NiN 3.0 kartografi: symboler for kartleggingsenheter (utkast A, erstattet av B)

Laget 07.10.2026 fra symboltabellene. Utskrift: A4 liggende.

Fastmarkssystemer og våtmarkssystemer: 388 i 1:5 000, 212 i 1:20 000, 116 i 1:50 000. Fyllfargen viser hovedtypen. Skravur og symboler viser kartleggingsenheten og er beregnet fra miljøvariablene som definerer enheten.

Hver tabell leses fra venstre mot høyre: en enhet i 1:50 000 deles i enhetene til høyre for den i 1:20 000, som igjen deles i 1:5 000. En egenskap tegnes bare i de målestokkene der den skiller enheter i hovedtypen. Derfor er symbolene enklest i 1:50 000. Symbolene er tegnet forstørret.

Tegnforklaring

De samme reglene gjelder i alle hovedtyper og i alle målestokker. En enhet som omfatter det laveste trinnet av en variabel, får ikke symbol for den: symbolet betyr at egenskapen gjelder hele enheten. Større symbol betyr høyere trinn. Tetthet brukes ikke til å vise grad.

Skravur



Skrå skravur
Kalkfattig



Skravur mot venstre
Skravuren sier ikke noe om kalkinnhold



Oransje skravur
Tørkeutsatt



Prikket skravur
Skiller to enheter som ellers ville fått likt symbol, uten egen betydning



Vannrett skravur
Intermediær



Blå skravur
Hele enheten er frisk eller sjelden tørrlagt



Mørk rød skravur
Svært tørkeutsatt



Loddrett skravur
Kalkrik



Grå skravur
Noe tørkeutsatt, eller spenner over det meste av skalaen




Stiplet skravur
Myrkant (hele enheten ligger i myrkant-delen av myrflatepreg)

Symboler



Sirkel i fargen til naturtypen marka ligner
rabbe, fjellhei, snøleie (hvit) eller skog (grønn)



Blå sirkel
vannsprut



Blå rute
type vanntilførsel



Mørk firkant
kornstørrelse, større firkant = grovere



Gulbrun rute
hevd



Brun trekant
naturlig gjødslet



Grønn sirkel
Skog i våtmark og sterkt endret skogsmark



Blå sirkel
kildevannspåvirket



Blå strek
overrislet



Blågrønt plusstegn
saltpåvirket



Mørk firkant
substrattype



Gulbrun trekant
gjødsling



Grå strek
vindutsatt



Blå sirkel
fuktig mark



Blått kryss
forstyrret av bølger eller strøm



Hvit sirkel
snøleiepreg



Mørk ring
type inngrep



Gulbrun trekant
åpning av tresjiktet



Brun stjerne
grad av sandstabilisering

Nyanser av fyllfargen

TG01 Nakne løsmasser har én nyanse av sandfargen per løsmassetype, i stedet for et eget symbol.



TG01 Stedegne løsmasser
Grunnfargen til hovedtypen



TG01 Breforland og snøavsmeltingsområde
Kjølig, gråbeige



TG01 Flomskredmateriale
Brun, beslektet med flomskredmark



TG01 Morene
Gråere og mørkere sand



TG01 Konsoliderte marine bresedimenter
Rosagrå leirfarge



TG01 Hevet strand
Lys, gul sand som strand




TG01 Historisk skred
Brun, beslektet med skred- og rasmark

T Fastmarkssystemer

TB01 Fastmarksskogsmark

1:50 000 · 2 enheter




TB01-01
Kalkfattig til intermediær skog
Kalkinnhold b,c,d,e,f: vannrett skravur


1:20 000 · 6 enheter




TB01-01
Blåbær-bærlyngskog
Kalkinnhold b,c: skrå skravur



TB01-02
Lågurt-bærlyng-lågurtskog
Kalkinnhold d,e,f: vannrett skravur



TB01-04
Lyng- og lavskog
Kalkinnhold b,c: skrå skravur. Uttørkingsfare e,f,g,h: mørk rød skravur



TB01-05
Lyng- og lav-lågurtskog
Kalkinnhold d,e,f: vannrett skravur. Uttørkingsfare e,f,g,h: mørk rød skravur

1:5 000 · 18 enheter




TB01-01
Blåbærskog
Kalkinnhold b,c: skrå skravur. Uttørkingsfare a,b: blå skravur




TB01-04
Bærlyngskog
Kalkinnhold b,c: skrå skravur. Uttørkingsfare c,d: grå skravur




TB01-13
Blåbærfuktskog
Kalkinnhold b,c: skrå skravur. Uttørkingsfare a,b: blå skravur. Vannmetning b,c: sirkel 1.0 mm



TB01-16
Lyngfuktskog
Kalkinnhold b,c: skrå skravur. Uttørkingsfare c,d,e,f: oransje skravur. Vannmetning b,c: sirkel 1.0 mm



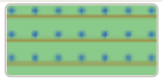
TB01-02
Lågurtskog
Kalkinnhold d,e,f: vannrett skravur. Uttørkingsfare a,b: blå skravur



TB01-05
Bærlyng-lågurtskog
Kalkinnhold d,e,f: vannrett skravur. Uttørkingsfare c,d: grå skravur



TB01-14
Storbregneskog
Kalkinnhold d,e,f: vannrett skravur. Uttørkingsfare a,b: blå skravur. Vannmetning b,c: sirkel 1.0 mm




TB01-17
Intermediær lyngfuktskog
Kalkinnhold d,e,f: vannrett skravur. Uttørkingsfare c,d,e,f: oransje skravur. Vannmetning b,c: sirkel 1.0 mm





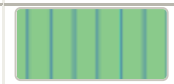


TB01-07
Lyngskog
Kalkinnhold b,c: skrå skravur. Uttørkingsfare e,f: oransje skravur




TB01-10
Lavskog
Kalkinnhold b,c: skrå skravur. Uttørkingsfare g,h: mørk rød skravur



TB01-08
Lyng-lågurtskog
Kalkinnhold d,e,f: vannrett skravur. Uttørkingsfare e,f: oransje skravur

1:50 000 · 2 enheter	1:20 000 · 6 enheter	1:5 000 · 18 enheter
		 **TB01-11** Lav-lågurtskog Kalkinnhold d,e,f: vannrett skravur. Uttørkingsfare g,h: mørk rød skravur
 **TB01-02** Kalkskog Kalkinnhold g,h,i: loddrett skravur	 **TB01-03** Frisk kalkskog og kalk-bærlyngskog Kalkinnhold g,h,i: loddrett skravur	 **TB01-03** Frisk kalkskog Kalkinnhold g,h,i: loddrett skravur. Uttørkingsfare a,b: blå skravur
		 **TB01-06** Kalk-bærlyngskog Kalkinnhold g,h,i: loddrett skravur. Uttørkingsfare c,d: grå skravur
		 **TB01-15** Høgstaudeskog Kalkinnhold g,h,i: loddrett skravur. Uttørkingsfare a,b: blå skravur. Vannmetning b,c: sirkel 1.0 mm
		 **TB01-18** Kalkrik lyngfuktskog Kalkinnhold g,h,i: loddrett skravur. Uttørkingsfare c,d,e,f: oransje skravur. Vannmetning b,c: sirkel 1.0 mm
	 **TB01-06** Kalklyng- og kalklavskog Kalkinnhold g,h,i: loddrett skravur. Uttørkingsfare e,f,g,h: mørk rød skravur	 **TB01-09** Kalk-lyngskog Kalkinnhold g,h,i: loddrett skravur. Uttørkingsfare e,f: oransje skravur
		 **TB01-12** Kalk-lavskog Kalkinnhold g,h,i: loddrett skravur. Uttørkingsfare g,h: mørk rød skravur

 TF01 Sand- og dyneskogsmark

1:50 000 · 1 enheter	1:20 000 · 2 enheter	1:5 000 · 2 enheter
 **TF01-01** Sand- og dyneskogsmark	 **TF01-01** Sandskogsmark Sandstabilisering k: stjerne 2.2 mm	 **TF01-01** Sandskogsmark Sandstabilisering k: stjerne 2.2 mm
	 **TF01-02** Dyneskogsmark Sandstabilisering j: stjerne 1.0 mm	 **TF01-02** Dyneskogsmark Sandstabilisering j: stjerne 1.0 mm

TF02 Flomskogsmark

Gjelder alle enheter: Blå skravur: flompåvirket.

1:50 000 · 2 enheter



TF02-01
Ferskvanns-flomskogsmark
Blå skravur: flompåvirket




TF02-02
Brakkvanns-flomskogsmark
Blå skravur: flompåvirket. Marin salinitet b,c,d: plusstegn 1.0 mm

1:20 000 · 2 enheter



TF02-01
Ferskvanns-flomskogsmark
Blå skravur: flompåvirket




TF02-02
Brakkvanns-flomskogsmark
Blå skravur: flompåvirket. Marin salinitet b,c,d: plusstegn 1.0 mm


1:5 000 · 6 enheter



TF02-01
Beskyttet flomskogsmark på finmateriale
Blå skravur: flompåvirket. Vannforstyrrelsesintensitet a,b,c: kryss 1.0 mm. Dominerende kornstørrelse A,B,C: firkant 1.0 mm




TF02-02
Noe eksponert flomskogsmark på finmateriale
Blå skravur: flompåvirket. Vannforstyrrelsesintensitet d,e: kryss 2.2 mm. Dominerende kornstørrelse A,B,C: firkant 1.0 mm




TF02-03
Kildevannspåvirket flomskogsmark på finmateriale
Blå skravur: flompåvirket. Kildevannspåvirkning b,c: sirkel 1.0 mm. Vannforstyrrelsesintensitet a,b,c,d,e: kryss 1.6 mm. Dominerende kornstørrelse A,B,C: firkant 1.0 mm



TF02-04
Beskyttet flomskogsmark på grus og stein
Blå skravur: flompåvirket. Vannforstyrrelsesintensitet a,b,c: kryss 1.0 mm. Dominerende kornstørrelse D,E: firkant 2.2 mm



TF02-05
Noe eksponert flomskogsmark på grus og stein
Blå skravur: flompåvirket. Vannforstyrrelsesintensitet d,e: kryss 2.2 mm. Dominerende kornstørrelse D,E: firkant 2.2 mm



TF02-06
Brakkvanns-flomskogsmark
Blå skravur: flompåvirket. Vannforstyrrelsesintensitet a,b,c,d,e: kryss 1.6 mm. Marin salinitet b,c,d: plusstegn 1.0 mm. Dominerende kornstørrelse A,B,C,D,E: firkant 1.6 mm


TI01 Klart endret skogsmark

1:50 000 · 1 enheter




TI01-01
Klart endret skogsmark

1:20 000 · 4 enheter




TI01-01
Grøftet eller markforstyrret klart endret ikke-kalkrik skog
Kalkinnhold b,c,d,e,f: vannrett skravur. Skilles fra naboenhet med prikket skravur

1:5 000 · 10 enheter









TI01-01
Grøftet eller markforstyrret klart endret friskere ikke-kalkrik skog
Kalkinnhold b,c,d,e,f: vannrett skravur. Uttørkingsfare a,b,c,d: grå skravur



TI01-03
Grøftet eller markforstyrret klart endret tørrere ikke-kalkrik skog
Kalkinnhold b,c,d,e,f: vannrett skravur. Uttørkingsfare e,f,g,h: mørk rød skravur








TI01-09
Klart endret storbregneskog
Kalkinnhold d,e,f: vannrett skravur. Uttørkingsfare a,b: blå skravur. Kildevannspåvirkning b,c: sirkel 1.0 mm

1:50 000 · 1 enheter	1:20 000 · 4 enheter	1:5 000 · 10 enheter
	 **TI01-02** Grøftet eller markforstyrret klart endret kalkskog Kalkinnhold g,h,i: loddrett skravur. Skilles fra naboenhet med prikket skravur	 **TI01-02** Grøftet eller markforstyrret klart endret friskere kalkskog Kalkinnhold g,h,i: loddrett skravur. Uttørkingsfare a,b,c,d: grå skravur
		 **TI01-04** Grøftet eller markforstyrret klart endret tørrere kalkskog Kalkinnhold g,h,i: loddrett skravur. Uttørkingsfare e,f,g,h: mørk rød skravur
		 **TI01-10** Klart endret høgstaudeskog Kalkinnhold g,h,i: loddrett skravur. Uttørkingsfare a,b: blå skravur. Kildevannspåvirkning b,c: sirkel 1.0 mm
	 **TI01-03** Hugd eller treslagstypeskiftet klart endret ikke-kalkrik skog Kalkinnhold b,c,d,e,f: vannrett skravur	 **TI01-05** Hugd eller treslagstypeskiftet klart endret friskere ikke-kalkrik skog Kalkinnhold b,c,d,e,f: vannrett skravur. Uttørkingsfare a,b,c,d: grå skravur. Skilles fra naboenhet med prikket skravur
		 **TI01-07** Hugd eller treslagstypeskiftet klart endret tørrere ikke-kalkrik skog Kalkinnhold b,c,d,e,f: vannrett skravur. Uttørkingsfare e,f,g,h: mørk rød skravur. Skilles fra naboenhet med prikket skravur
	 **TI01-04** Hugd eller treslagstypeskiftet klart endret kalkskog Kalkinnhold g,h,i: loddrett skravur	 **TI01-06** Hugd eller treslagstypeskiftet klart endret friskere kalkskog Kalkinnhold g,h,i: loddrett skravur. Uttørkingsfare a,b,c,d: grå skravur. Skilles fra naboenhet med prikket skravur
		 **TI01-08** Hugd eller treslagstypeskiftet klart endret tørrere kalkskog Kalkinnhold g,h,i: loddrett skravur. Uttørkingsfare e,f,g,h: mørk rød skravur. Skilles fra naboenhet med prikket skravur






TM06 Sterkt endret skogsmark

Gjelder alle enheter: Grønn sirkel: sterkt endret mark som oppfattes som skog.

1:50 000 · 2 enheter	1:20 000 · 2 enheter	1:5 000 · 3 enheter
 **TM06-01** Sterkt endret skogsmark Grønn sirkel: sterkt endret mark som oppfattes som skog	 **TM06-01** Sterkt endret skogsmark etter markinngrep Grønn sirkel: sterkt endret mark som oppfattes som skog	 **TM06-01** Sterkt endret skogsmark etter markinngrep Grønn sirkel: sterkt endret mark som oppfattes som skog
 **TM06-02** Sterkt endret skogsmark i mellomsuksesjonsstadium Grønn sirkel: sterkt endret mark som oppfattes som skog. Skilles fra naboenhet med symbol: vinkel 1.0 mm	 **TM06-02** Sterkt endret skogsmark i mellomsuksesjonsstadium Grønn sirkel: sterkt endret mark som oppfattes som skog. Skilles fra naboenhet med symbol: vinkel 1.0 mm	 **TM06-02** Mellomsuksesjonsstadium som ikke har opphav i skogsmark Grønn sirkel: sterkt endret mark som oppfattes som skog. Skilles fra naboenhet med symbol: vinkel 1.0 mm

1:50 000 · 2 enheter	1:20 000 · 2 enheter	1:5 000 · 3 enheter
		 **TM06-03** Mellomsuksesjonsstadium i skogsmark Grønn sirkel: sterkt endret mark som oppfattes som skog. Skilles fra naboenhet med symbol: stjerne 1.0 mm

TA03 Arktisk-alpin hei og leside

1:50 000 · 2 enheter	1:20 000 · 7 enheter	1:5 000 · 16 enheter
 **TA03-01** Kalkfattig til litt kalkrik arktisk-alpin hei og leside Kalkinnhold b,c,d,e,f: vannrett skravur	 **TA03-01** Kalkfattig leside Kalkinnhold b,c: skrå skravur. Uttørkingsfare b,c: grå skravur	 **TA03-01** Kalkfattig leside Kalkinnhold b,c: skrå skravur. Uttørkingsfare b,c: grå skravur
	 **TA03-02** Intermediær til litt kalkrik leside Kalkinnhold d,e,f: vannrett skravur. Uttørkingsfare b,c: grå skravur	 **TA03-02** Intermediær til litt kalkrik leside Kalkinnhold d,e,f: vannrett skravur. Uttørkingsfare b,c: grå skravur
		 **TA03-12** Storbregne-fjelleng Kalkinnhold d,e,f: vannrett skravur. Uttørkingsfare b,c: grå skravur. Vannmetning b,c: sirkel 1.0 mm
	 **TA03-04** Kalkfattig fjell-lavhei og -lynghei Kalkinnhold b,c: skrå skravur. Uttørkingsfare d,e,f,g: oransje skravur	 **TA03-04** Kalkfattig fjell-lynghei Kalkinnhold b,c: skrå skravur. Uttørkingsfare d,e: oransje skravur
		 **TA03-08** Kalkfattig fjell-lavhei Kalkinnhold b,c: skrå skravur. Uttørkingsfare f,g: mørk rød skravur
		 **TA03-14** Kalkfattig fjell-fukthei Kalkinnhold b,c: skrå skravur. Uttørkingsfare d,e: oransje skravur. Vannmetning b,c: sirkel 1.0 mm
	 **TA03-05** Intermediær til litt kalkrik fjell-lavhei og -lynghei Kalkinnhold d,e,f: vannrett skravur. Uttørkingsfare d,e,f,g: oransje skravur	 **TA03-05** Intermediær til litt kalkrik fjell-lynghei Kalkinnhold d,e,f: vannrett skravur. Uttørkingsfare d,e: oransje skravur
		 **TA03-09** Intermediær til litt kalkrik fjell-lavhei Kalkinnhold d,e,f: vannrett skravur. Uttørkingsfare f,g: mørk rød skravur
		 **TA03-15** Intermediær til svakt kalkfattig fjell-fukthei Kalkinnhold d,e,f: vannrett skravur. Uttørkingsfare d,e: oransje skravur. Vannmetning b,c: sirkel 1.0 mm
 **TA03-02** Kalkrik til saltanriket arktisk-alpin hei og leside Kalkinnhold g,h,i,j: loddrett skravur	 **TA03-03** Temmelig til ekstremt kalkrik leside Kalkinnhold g,h,i: loddrett skravur. Uttørkingsfare b,c: grå skravur	 **TA03-03** Temmelig til ekstremt kalkrik leside Kalkinnhold g,h,i: loddrett skravur. Uttørkingsfare b,c: grå skravur

1:50 000 · 2 enheter	1:20 000 · 7 enheter	1:5 000 · 16 enheter
		TA03-13 Høgstaude-fjelleng Kalkinnhold g,h,i: loddrett skravur. Uttørkingsfare b,c: grå skravur. Vannmetning b,c: sirkel 1.0 mm
	TA03-06 Temmelig til ekstremt kalkrik fjell-lavhei og -lynghei Kalkinnhold g,h,i: loddrett skravur. Uttørkingsfare d,e,f,g: oransje skravur	**TA03-06** Temmelig til ekstremt kalkrik fjell-lynghei Kalkinnhold g,h,i: loddrett skravur. Uttørkingsfare d,e: oransje skravur
		TA03-10 Temmelig til ekstremt kalkrik fjell-lavhei Kalkinnhold g,h,i: loddrett skravur. Uttørkingsfare f,g: mørk rød skravur
		TA03-16 Kalkrik fjell-fukteng Kalkinnhold g,h,i: loddrett skravur. Uttørkingsfare d,e: oransje skravur. Vannmetning b,c: sirkel 1.0 mm
	TA03-07 Saltanriket ekstremrik fjell-lavhei og -lynghei Kalkinnhold j: loddrett skravur. Uttørkingsfare d,e,f,g: oransje skravur. Skilles fra naboenhet med prikket skravur	**TA03-07** Saltanriket ekstremrik fjell-lynghei Kalkinnhold j: loddrett skravur. Uttørkingsfare d,e: oransje skravur. Skilles fra naboenhet med prikket skravur
		TA03-11 Saltanriket ekstremrik fjell-lavhei Kalkinnhold j: loddrett skravur. Uttørkingsfare f,g: mørk rød skravur. Skilles fra naboenhet med prikket skravur

TA04 Arktisk-alpin grasmark

1:50 000 · 2 enheter	1:20 000 · 3 enheter	1:5 000 · 3 enheter
TA04-01 Kalkfattig til litt kalkrik arktisk-alpin grasmark Kalkinnhold b,c,d,e,f: vannrett skravur	**TA04-01** Kalkfattig arktisk-alpin grasmark Kalkinnhold b,c: skrå skravur	**TA04-01** Kalkfattig arktisk-alpin grasmark Kalkinnhold b,c: skrå skravur
	TA04-02 Intermediær til litt kalkrik arktisk-alpin grasmark Kalkinnhold d,e,f: vannrett skravur	**TA04-02** Intermediær til litt kalkrik arktisk-alpin grasmark Kalkinnhold d,e,f: vannrett skravur
TA04-02 Klart kalkrik arktisk-alpin grasmark Kalkinnhold g,h,i: loddrett skravur	**TA04-03** Temmelig til ekstremt kalkrik arktisk-alpin grasmark Kalkinnhold g,h,i: loddrett skravur	**TA04-03** Temmelig til ekstremt kalkrik arktisk-alpin grasmark Kalkinnhold g,h,i: loddrett skravur

TD06 Rabbe

1:50 000 · 2 enheter	1:20 000 · 4 enheter	1:5 000 · 4 enheter
TD06-01 Kalkfattig til litt kalkrik rabbe Kalkinnhold b,c,d,e,f: vannrett skravur. Vindutsatthet b,c,y: strek 1.6 mm	**TD06-01** Kalkfattig rabbe Kalkinnhold b,c: skrå skravur. Vindutsatthet b,c,y: strek 1.6 mm	**TD06-01** Kalkfattig rabbe Kalkinnhold b,c: skrå skravur. Vindutsatthet b,c,y: strek 1.6 mm



1:50 000 · 2 enheter	1:20 000 · 4 enheter	1:5 000 · 4 enheter
	TD06-02 Intermediær til litt kalkrik rabbe Kalkinnhold d,e,f: vannrett skravur. Vindutsatthet b,c: strek 1.0 mm	**TD06-02** Intermediær til litt kalkrik rabbe Kalkinnhold d,e,f: vannrett skravur. Vindutsatthet b,c: strek 1.0 mm
TD06-02 Klart kalkrik til saltanriket ekstremrik rabbe Kalkinnhold g,h,i,j: loddrett skravur. Vindutsatthet b,c: strek 1.0 mm	**TD06-03** Klart kalkrik rabbe Kalkinnhold g,h,i: loddrett skravur. Vindutsatthet b,c: strek 1.0 mm	**TD06-03** Klart kalkrik rabbe Kalkinnhold g,h,i: loddrett skravur. Vindutsatthet b,c: strek 1.0 mm
	TD06-04 Saltanriket ekstremrik rabbe Kalkinnhold j: loddrett skravur. Vindutsatthet b,c: strek 1.0 mm. Skilles fra naboenhet med prikket skravur	**TD06-04** Saltanriket ekstremrik rabbe Kalkinnhold j: loddrett skravur. Vindutsatthet b,c: strek 1.0 mm. Skilles fra naboenhet med prikket skravur

TC08 Snøleie

1:50 000 · 2 enheter	1:20 000 · 5 enheter	1:5 000 · 9 enheter
TC08-01 Kalkfattig til litt kalkrikt moderat til ekstremt snøleie Snødekkebetinget vekstsesongreduksjon a,b,c,d,e,f,g: sirkel 1.6 mm	**TC08-01** Kalkfattig moderat til seint snøleie Kalkinnhold b,c: skrå skravur. Snødekkebetinget vekstsesongreduksjon a,b,c,d: sirkel 1.6 mm	**TC08-01** Kalkfattig moderat snøleie Kalkinnhold b,c: skrå skravur. Snødekkebetinget vekstsesongreduksjon a,b: sirkel 1.0 mm
		TC08-04 Kalkfattig seint snøleie Kalkinnhold b,c: skrå skravur. Snødekkebetinget vekstsesongreduksjon c,d: sirkel 2.2 mm
	TC08-02 Intermediært til litt kalkrikt moderat til seint snøleie Kalkinnhold d,e,f: vannrett skravur. Snødekkebetinget vekstsesongreduksjon a,b,c,d: sirkel 1.6 mm	**TC08-02** Intermediært til litt kalkrikt moderat snøleie Kalkinnhold d,e,f: vannrett skravur. Snødekkebetinget vekstsesongreduksjon a,b: sirkel 1.0 mm
		TC08-05 Intermediært til litt kalkrikt seint snøleie Kalkinnhold d,e,f: vannrett skravur. Snødekkebetinget vekstsesongreduksjon c,d: sirkel 2.2 mm
	TC08-04 Fattig til litt kalkrikt ekstrem-snøleie	**TC08-07** Fattig til litt kalkrikt ekstrem-snøleie Kalkinnhold b,c,d,e,f: vannrett skravur. Snødekkebetinget vekstsesongreduksjon e,f: sirkel 2.2 mm
		TC08-09 Vegetasjonsfritt snøleie
TC08-02 Sterkt kalkrikt moderat til ekstremt snøleie Kalkinnhold g,h,i: loddrett skravur. Snødekkebetinget vekstsesongreduksjon a,b,c,d,e,f: sirkel 1.0 mm	**TC08-03** Sterkt kalkrikt moderat til seint snøleie Kalkinnhold g,h,i: loddrett skravur. Snødekkebetinget vekstsesongreduksjon a,b,c,d: sirkel 1.6 mm	**TC08-03** Sterkt kalkrikt moderat snøleie Kalkinnhold g,h,i: loddrett skravur. Snødekkebetinget vekstsesongreduksjon a,b: sirkel 1.0 mm
		TC08-06 Sterkt kalkrikt seint snøleie Kalkinnhold g,h,i: loddrett skravur. Snødekkebetinget vekstsesongreduksjon c,d: sirkel 2.2 mm




1:50 000 · 2 enheter	1:20 000 · 5 enheter	1:5 000 · 9 enheter
	 **TC08-05** Sterkt kalkrikt ekstrem-snøleie Kalkinnhold g,h,i: loddrett skravur. Snødekkebetinget vekstsesongreduksjon e,f: sirkel 2.2 mm	 **TC08-08** Sterkt kalkrikt ekstrem-snøleie Kalkinnhold g,h,i: loddrett skravur. Snødekkebetinget vekstsesongreduksjon e,f: sirkel 2.2 mm

TD05 Naturlig beitebetinget eng

1:50 000 · 1 enheter	1:20 000 · 2 enheter	1:5 000 · 2 enheter
 **TD05-01** Naturlig beitebetinget eng	 **TD05-01** Sterkt intermediær til litt kalkrik naturlig beitebetinget eng Kalkinnhold e,f: vannrett skravur	 **TD05-01** Sterkt intermediær til litt kalkrik naturlig beitebetinget eng Kalkinnhold e,f: vannrett skravur
	 **TD05-02** Klart kalkrik naturlig beitebetinget eng Kalkinnhold g,h,i: loddrett skravur	 **TD05-02** Klart kalkrik naturlig beitebetinget eng Kalkinnhold g,h,i: loddrett skravur

TE08 Flommarkseng

Gjelder alle enheter: Blå skravur: flompåvirket.

1:50 000 · 1 enheter	1:20 000 · 2 enheter	1:5 000 · 4 enheter
 **TE08-01** Flommarkseng Blå skravur: flompåvirket	 **TE08-01** Intermediær til litt kalkrik flommarkseng Kalkinnhold d,e,f: vannrett skravur. Blå skravur: flompåvirket	 **TE08-01** Intermediær til litt kalkrik flommarkseng Kalkinnhold d,e,f: vannrett skravur. Blå skravur: flompåvirket
		 **TE08-03** Intermediær til litt kalkrik flommarkseng med kildevannspåvirkning Kalkinnhold d,e,f: vannrett skravur. Blå skravur: flompåvirket. Kildevannspåvirkning b,c: sirkel 1.0 mm
	 **TE08-02** Klart kalkrik flommarkseng Kalkinnhold g,h: loddrett skravur. Blå skravur: flompåvirket	 **TE08-02** Klart kalkrik flommarkseng Kalkinnhold g,h: loddrett skravur. Blå skravur: flompåvirket
		 **TE08-04** Klart kalkrik flommarkseng med kildevannspåvirkning Kalkinnhold g,h: loddrett skravur. Blå skravur: flompåvirket. Kildevannspåvirkning b,c: sirkel 1.0 mm

TD04 Fosse-eng

Gjelder alle enheter: Blå skravur: fossesprut.

1:50 000 · 1 enheter



TD04-01
Fosse-eng
Blå skravur: fossesprut

1:20 000 · 4 enheter



TD04-01
Intermediær til litt kalkrik fosse-eng med fossestøv og -tåkepreg
Kalkinnhold d,e,f: vannrett skravur. Blå skravur: fossesprut.
Vannsprutintensitet b,c: sirkel 1.0 mm



TD04-02
Klart kalkrik fosse-eng med fossestøv og -tåkepreg
Kalkinnhold g,h: loddrett skravur. Blå skravur: fossesprut.
Vannsprutintensitet b,c: sirkel 1.0 mm



TD04-03
Intermediær til litt kalkrik fosse-eng med fosseyrpreg
Kalkinnhold d,e,f,g,h: vannrett skravur. Blå skravur: fossesprut.
Vannsprutintensitet d,e: sirkel 1.0 mm



TD04-04
Klart kalkrik fosse-eng med fosseyrpreg
Kalkinnhold g,h: loddrett skravur. Blå skravur: fossesprut.
Vannsprutintensitet d: sirkel 2.2 mm

1:5 000 · 5 enheter



TD04-01
Intermediær til litt kalkrik fosse-eng med fossestøv og -tåkepreg
Kalkinnhold d,e,f: vannrett skravur. Blå skravur: fossesprut.
Vannsprutintensitet b,c: sirkel 1.0 mm



TD04-02
Klart kalkrik fosse-eng med fossestøv og -tåkepreg
Kalkinnhold g,h: loddrett skravur. Blå skravur: fossesprut.
Vannsprutintensitet b,c: sirkel 1.0 mm



TD04-03
Intermediær til litt kalkrik fosse-eng med fosseyrpreg
Kalkinnhold d,e,f: vannrett skravur. Blå skravur: fossesprut.
Vannsprutintensitet d: sirkel 2.2 mm




TD04-05
Fosse-eng med fosseregnpreg
Kalkinnhold d,e,f,g,h: vannrett skravur. Blå skravur: fossesprut.
Vannsprutintensitet e: sirkel 1.6 mm



TD04-04
Klart kalkrik fosse-eng med fosseyrpreg
Kalkinnhold g,h: loddrett skravur. Blå skravur: fossesprut.
Vannsprutintensitet d: sirkel 2.2 mm

TC05 Strandeng

1:50 000 · 2 enheter




TC05-01
Strandeng
Marin salinitet f,g,h: plusstegn 1.6 mm




TC05-02
Brakkvanns-strandeng
Tørrleggingsvarighet c,d,e,f,g,h: oransje skravur. Marin salinitet b,c,d,e: plusstegn 1.0 mm

1:20 000 · 2 enheter



TC05-01
Strandeng
Marin salinitet f,g,h: plusstegn 1.6 mm



TC05-02
Brakkvanns-strandeng
Tørrleggingsvarighet c,d,e,f,g,h: oransje skravur. Marin salinitet b,c,d,e: plusstegn 1.0 mm

1:5 000 · 3 enheter



TC05-01
Strandeng i nederste- til midtre landstrandbelte
Tørrleggingsvarighet c,d,e,f,g,h: oransje skravur. Marin salinitet f,g,h: plusstegn 1.6 mm



TC05-02
Strandeng i øverste landstrandbelte til bølgebeltet
Tørrleggingsvarighet g,h,i,j,k: mørk rød skravur. Marin salinitet f,g,h: plusstegn 1.6 mm



TC05-03
Brakkvanns-strandeng
Tørrleggingsvarighet c,d,e,f,g,h: oransje skravur. Marin salinitet b,c,d,e: plusstegn 1.0 mm

TC06 Fuglefjell-eng

1:50 000 · 1 enheter



TC06-01
Fuglefjell-eng

1:20 000 · 1 enheter



TC06-01
Fuglefjell-eng

1:5 000 · 3 enheter



TC06-01
Klart naturlig gjødslingspreget fuglefjell-eng
Naturlig gjødsling b,c: trekant 1.0 mm



TC06-02
Sterkt naturlig til overgjødslet fuglefjell-eng
Naturlig gjødsling d,y: trekant 1.0 mm



TC06-03
Høgstaude-fuglefjelleng
Kildevannspåvirkning b,c: sirkel 1.0 mm. Naturlig gjødsling b,c,d: trekant 1.6 mm

TC07 Fugletopp

1:50 000 · 1 enheter



TC07-01
Fugletopp

1:20 000 · 1 enheter



TC07-01
Fugletopp

1:5 000 · 1 enheter



TC07-01
Fugletopp

TK01 Semi-naturlig eng

1:50 000 · 2 enheter



TK01-01
Kalkfattig til svakt kalkrik åpen semi-naturlig eng
Kalkinnhold b,c,d,e,f: vannrett skravur. Sandstabilisering j,k,y: stjerne 2.2 mm

1:20 000 · 7 enheter



TK01-01
Kalkfattig semi-naturlig eng med åpent tresjikt
Kalkinnhold b,c: skrå skravur. Sandstabilisering j,k,y: stjerne 2.2 mm

1:5 000 · 27 enheter



TK01-01
Kalkfattig semi-naturlig eng uten markrydding med åpent tresjikt
Kalkinnhold b,c: skrå skravur. Uttørkingsfare a,b,c: grå skravur. Sandstabilisering j,k,y: stjerne 2.2 mm





TK01-04
Kalkfattig semi-naturlig ikke markryddet tørreng med åpent tresjikt
Kalkinnhold b,c: skrå skravur. Uttørkingsfare d,e,f,g: oransje skravur. Sandstabilisering j,k,y: stjerne 2.2 mm





TK01-07
Kalkfattig semi-naturlig markryddet eng med åpent tresjikt
Kalkinnhold b,c: skrå skravur. Uttørkingsfare a,b,c: grå skravur. Markbearbeidingsintensitet a,b: rute 1.0 mm. Sandstabilisering j,k,y: stjerne 2.2 mm



TK01-10
Kalkfattig semi-naturlig markryddet tørreng med åpent tresjikt
Kalkinnhold b,c: skrå skravur. Uttørkingsfare d,e,f,g: oransje skravur. Markbearbeidingsintensitet a,b: rute 1.0 mm. Sandstabilisering j,k,y: stjerne 2.2 mm

1:50 000 · 2 enheter	1:20 000 · 7 enheter	1:5 000 · 27 enheter
	 **TK01-02** Svakt kalkrik semi-naturlig eng med åpent tresjikt Kalkinnhold d,e,f: vannrett skravur. Sandstabilisering j,k,y: stjerne 2.2 mm	 **TK01-02** Svakt kalkrik semi-naturlig ikke markryddet eng med åpent tresjikt Kalkinnhold d,e,f: vannrett skravur. Uttørkingsfare a,b,c: grå skravur. Sandstabilisering j,k,y: stjerne 2.2 mm
		 **TK01-05** Svakt kalkrik semi-naturlig ikke markryddet tørreng med åpent tresjikt Kalkinnhold d,e,f: vannrett skravur. Uttørkingsfare d,e,f,g: oransje skravur. Sandstabilisering j,k,y: stjerne 2.2 mm
		 **TK01-08** Svakt kalkrik semi-naturlig markryddet eng med åpent tresjikt Kalkinnhold d,e,f: vannrett skravur. Uttørkingsfare a,b,c: grå skravur. Markbearbeidingsintensitet a,b: rute 1.0 mm. Sandstabilisering j,k,y: stjerne 2.2 mm
		 **TK01-11** Svakt kalkrik semi-naturlig markryddet tørreng med åpent tresjikt Kalkinnhold d,e,f: vannrett skravur. Uttørkingsfare d,e,f,g: oransje skravur. Markbearbeidingsintensitet a,b: rute 1.0 mm. Sandstabilisering j,k,y: stjerne 2.2 mm
		 **TK01-25** Svakt kalkrik kildevannspåvirket semi-naturlig fukteng Kalkinnhold d,e,f: vannrett skravur. Uttørkingsfare a,b,c: grå skravur. Kildevannspåvirkning b,c: sirkel 1.0 mm. Sandstabilisering j,k,y: stjerne 2.2 mm
	 **TK01-04** Kalkfattig åpen semi-naturlig eng Kalkinnhold b,c: skrå skravur. Åpning av tresjiktet y: trekant 1.0 mm. Sandstabilisering j,k,y: stjerne 2.2 mm	 **TK01-13** Kalkfattig åpen semi-naturlig ikke markryddet eng Kalkinnhold b,c: skrå skravur. Uttørkingsfare a,b,c: grå skravur. Åpning av tresjiktet y: trekant 1.0 mm. Sandstabilisering j,k,y: stjerne 2.2 mm
		 **TK01-16** Kalkfattig åpen semi-naturlig ikke markryddet tørreng Kalkinnhold b,c: skrå skravur. Uttørkingsfare d,e,f,g: oransje skravur. Åpning av tresjiktet y: trekant 1.0 mm. Sandstabilisering j,k,y: stjerne 2.2 mm
		 **TK01-19** Kalkfattig åpen semi-naturlig markryddet eng Kalkinnhold b,c: skrå skravur. Uttørkingsfare a,b,c: grå skravur. Markbearbeidingsintensitet a,b: rute 1.0 mm. Åpning av tresjiktet y: trekant 1.0 mm. Sandstabilisering j,k,y: stjerne 2.2 mm
		 **TK01-22** Kalkfattig åpen semi-naturlig markryddet tørreng Kalkinnhold b,c: skrå skravur. Uttørkingsfare d,e,f,g: oransje skravur. Markbearbeidingsintensitet a,b: rute 1.0 mm. Åpning av tresjiktet y: trekant 1.0 mm. Sandstabilisering j,k,y: stjerne 2.2 mm

1:50 000 · 2 enheter	1:20 000 · 7 enheter	1:5 000 · 27 enheter
	 **TK01-05** Svakt kalkrik åpen semi-naturlig eng Kalkinnhold d,e,f: vannrett skravur. Åpning av tresjiktet y: trekant 1.0 mm. Sandstabilisering j,k,y: stjerne 2.2 mm	 **TK01-14** Svakt kalkrik åpen semi-naturlig ikke markryddet eng Kalkinnhold d,e,f: vannrett skravur. Uttørkingsfare a,b,c: grå skravur. Åpning av tresjiktet y: trekant 1.0 mm. Sandstabilisering j,k,y: stjerne 2.2 mm
		 **TK01-17** Svakt kalkrik åpen semi-naturlig ikke markryddet tørreng Kalkinnhold d,e,f: vannrett skravur. Uttørkingsfare d,e,f,g: oransje skravur. Åpning av tresjiktet y: trekant 1.0 mm. Sandstabilisering j,k,y: stjerne 2.2 mm
		 **TK01-20** Svakt kalkrik åpen semi-naturlig markryddet eng Kalkinnhold d,e,f: vannrett skravur. Uttørkingsfare a,b,c: grå skravur. Markbearbeidingsintensitet a,b: rute 1.0 mm. Åpning av tresjiktet y: trekant 1.0 mm. Sandstabilisering j,k,y: stjerne 2.2 mm
		 **TK01-23** Svakt kalkrik åpen semi-naturlig markryddet tørreng Kalkinnhold d,e,f: vannrett skravur. Uttørkingsfare d,e,f,g: oransje skravur. Markbearbeidingsintensitet a,b: rute 1.0 mm. Åpning av tresjiktet y: trekant 1.0 mm. Sandstabilisering j,k,y: stjerne 2.2 mm
 **TK01-02** Klart kalkrik åpen semi-naturlig eng Kalkinnhold f,g,h,i: loddrett skravur. Sandstabilisering g,h,i,j,k,y: stjerne 1.6 mm	 **TK01-03** Klart kalkrik semi-naturlig eng med åpent tresjikt Kalkinnhold g,h,i: loddrett skravur. Sandstabilisering j,k,y: stjerne 2.2 mm	 **TK01-03** Klart kalkrik semi-naturlig ikke markryddet eng med åpent tresjikt Kalkinnhold g,h,i: loddrett skravur. Uttørkingsfare a,b,c: grå skravur. Sandstabilisering j,k,y: stjerne 2.2 mm
		 **TK01-06** Klart kalkrik semi-naturlig ikke markryddet tørreng med åpent tresjikt Kalkinnhold g,h,i: loddrett skravur. Uttørkingsfare d,e,f,g: oransje skravur. Sandstabilisering j,k,y: stjerne 2.2 mm
		 **TK01-09** Klart kalkrik semi-naturlig markryddet eng med åpent tresjikt Kalkinnhold g,h,i: loddrett skravur. Uttørkingsfare a,b,c: grå skravur. Markbearbeidingsintensitet a,b: rute 1.0 mm. Sandstabilisering j,k,y: stjerne 2.2 mm
		 **TK01-12** Klart kalkrik semi-naturlig markryddet tørreng med åpent tresjikt Kalkinnhold g,h,i: loddrett skravur. Uttørkingsfare d,e,f,g: oransje skravur. Markbearbeidingsintensitet a,b: rute 1.0 mm. Sandstabilisering j,k,y: stjerne 2.2 mm
		 **TK01-26** Klart kalkrik kildevannspåvirket semi-naturlig fukteng Kalkinnhold g,h,i: loddrett skravur. Uttørkingsfare a,b,c: grå skravur. Kildevannspåvirkning b,c: sirkel 1.0 mm. Sandstabilisering j,k,y: stjerne 2.2 mm

1:50 000 · 2 enheter	1:20 000 · 7 enheter	1:5 000 · 27 enheter
	TK01-06 Klart kalkrik åpen semi-naturlig eng Kalkinnhold g,h,i: loddrett skravur. Åpning av tresjiktet y: trekant 1.0 mm. Sandstabilisering j,k,y: stjerne 2.2 mm	**TK01-15** Klart kalkrik åpen semi-naturlig ikke markryddet eng Kalkinnhold g,h,i: loddrett skravur. Uttørkingsfare a,b,c: grå skravur. Åpning av tresjiktet y: trekant 1.0 mm. Sandstabilisering j,k,y: stjerne 2.2 mm
		TK01-18 Klart kalkrik åpen semi-naturlig ikke markryddet tørreng Kalkinnhold g,h,i: loddrett skravur. Uttørkingsfare d,e,f,g: oransje skravur. Åpning av tresjiktet y: trekant 1.0 mm. Sandstabilisering j,k,y: stjerne 2.2 mm
		TK01-21 Klart kalkrik åpen semi-naturlig markryddet eng Kalkinnhold g,h,i: loddrett skravur. Uttørkingsfare a,b,c: grå skravur. Markbearbeidingsintensitet a,b: rute 1.0 mm. Åpning av tresjiktet y: trekant 1.0 mm. Sandstabilisering j,k,y: stjerne 2.2 mm
		TK01-24 Klart kalkrik åpen semi-naturlig markryddet tørreng Kalkinnhold g,h,i: loddrett skravur. Uttørkingsfare d,e,f,g: oransje skravur. Markbearbeidingsintensitet a,b: rute 1.0 mm. Åpning av tresjiktet y: trekant 1.0 mm. Sandstabilisering j,k,y: stjerne 2.2 mm
	TK01-07 Kalkrik åpen semi-naturlig eng på stabilisert sand Kalkinnhold f,g,h,i: loddrett skravur. Uttørkingsfare d,e,f,g: oransje skravur. Åpning av tresjiktet y: trekant 1.0 mm. Sandstabilisering g,h,i: stjerne 1.0 mm	**TK01-27** Kalkrik åpen semi-naturlig eng på stabilisert sand Kalkinnhold f,g,h,i: loddrett skravur. Uttørkingsfare d,e,f,g: oransje skravur. Åpning av tresjiktet y: trekant 1.0 mm. Sandstabilisering g,h,i: stjerne 1.0 mm

TK02 Semi-naturlig strandeng

1:50 000 · 1 enheter	1:20 000 · 1 enheter	1:5 000 · 2 enheter
TK02-01 Semi-naturlig strandeng	**TK02-01** Semi-naturlig strandeng	**TK02-01** Semi-naturlig strandeng på uorganisk substrat
		TK02-02 Semi-naturlig strandeng på skjellsand Substrattype A: firkant 1.0 mm

TL01 Ny eng med semi-naturlig preg

1:50 000 · 2 enheter	1:20 000 · 3 enheter	1:5 000 · 8 enheter
TL01-01 Kalkfattig til litt kalkrik ny eng med semi-naturlig preg Kalkinnhold b,c,d,e,f: vannrett skravur	**TL01-01** Kalkfattig ny eng med semi-naturlig preg Kalkinnhold b,c: skrå skravur	**TL01-01** Kalkfattig frisk ny eng med semi-naturlig preg Kalkinnhold b,c: skrå skravur. Uttørkingsfare a,b,c: grå skravur
		TL01-04 Kalkfattig, intermediær til tørkeutsatt ny eng med semi-naturlig preg Kalkinnhold b,c: skrå skravur. Uttørkingsfare d,e,f,g: oransje skravur

1:50 000 · 2 enheter	1:20 000 · 3 enheter	1:5 000 · 8 enheter
	TL01-02 Intermediær til litt kalkrik ny eng med semi-naturlig preg Kalkinnhold d,e,f: vannrett skravur	**TL01-02** Intermediær til litt kalkrik frisk ny eng med semi-naturlig preg Kalkinnhold d,e,f: vannrett skravur. Uttørkingsfare a,b,c: grå skravur
		TL01-05 Intermediær til litt kalkrik, intermediær til tørkeutsatt ny eng med semi-naturlig preg Kalkinnhold d,e,f: vannrett skravur. Uttørkingsfare d,e,f,g: oransje skravur
		TL01-07 Intermediær til litt kalkrik frisk ny eng med semi-naturlig preg med klar kildevannspåvirkning Kalkinnhold d,e,f: vannrett skravur. Uttørkingsfare a,b,c: grå skravur. Kildevannspåvirkning b,c: sirkel 1.0 mm
TL01-02 Sterkt kalkrik ny eng med semi-naturlig preg Kalkinnhold g,h,i: loddrett skravur	**TL01-03** Sterkt kalkrik ny eng med semi-naturlig preg Kalkinnhold g,h,i: loddrett skravur	**TL01-03** Sterkt kalkrik frisk ny eng med semi-naturlig preg Kalkinnhold g,h,i: loddrett skravur. Uttørkingsfare a,b,c: grå skravur
		TL01-06 Sterkt kalkrik, intermediær til tørkeutsatt ny eng med semi-naturlig preg Kalkinnhold g,h,i: loddrett skravur. Uttørkingsfare d,e,f,g: oransje skravur
		TL01-08 Sterkt kalkrik frisk ny eng med semi-naturlig preg med klar kildevannspåvirkning Kalkinnhold g,h,i: loddrett skravur. Uttørkingsfare a,b,c: grå skravur. Kildevannspåvirkning b,c: sirkel 1.0 mm

TN02 Blomsterenger, usprøytete vegkanter og liknende med semi-naturlig hevdpreg

1:50 000 · 1 enheter	1:20 000 · 1 enheter	1:5 000 · 1 enheter
TN02-01 Blomsterenger, usprøytete vegkanter og liknende med semi-naturlig hevdpreg	**TN02-01** Blomsterenger, usprøytete vegkanter og liknende med semi-naturlig hevdpreg	**TN02-01** Blomsterenger, usprøytete vegkanter og liknende med semi-naturlig hevdpreg

TK03 Kystlynghei


1:50 000 · 2 enheter	1:20 000 · 3 enheter	1:5 000 · 8 enheter
TK03-01 Kalkfattig til litt kalkrik bakli-hei og kystlynghei Kalkinnhold b,c,d,e,f: vannrett skravur	**TK03-01** Kalkfattig bakli-hei og kystlynghei Kalkinnhold b,c: skrå skravur	**TK03-01** Kalkfattig bakli-hei Kalkinnhold b,c: skrå skravur. Uttørkingsfare b,c: grå skravur
		TK03-03 Kalkfattig veldrenert til vekselfuktig kystlynghei Kalkinnhold b,c: skrå skravur. Uttørkingsfare d,e,f,g: oransje skravur

1:50 000 · 2 enheter



TK03-02
Sterkt kalkrik kystlynghei
Kalkinnhold g,h,i: loddrett skravur. Uttørkingsfare d,e,f,g: oransje skravur

1:20 000 · 3 enheter



TK03-02
Intermediær til litt kalkrik bakli-hei og kystlynghei
Kalkinnhold d,e,f: vannrett skravur



TK03-03
Sterkt kalkrik kystlynghei
Kalkinnhold g,h,i: loddrett skravur. Uttørkingsfare d,e,f,g: oransje skravur


1:5 000 · 8 enheter



TK03-06
Kalkfattig fukt-kystlynghei
Kalkinnhold b,c: skrå skravur. Uttørkingsfare d,e,f,g: oransje skravur. Vannmetning b,c: sirkel 1.0 mm



TK03-02
Intermediær til litt kalkrik bakli-hei
Kalkinnhold d,e,f: vannrett skravur. Uttørkingsfare b,c: grå skravur



TK03-04
Intermediær til litt kalkrik veldrenert-vekselfuktig kystlynghei
Kalkinnhold d,e,f: vannrett skravur. Uttørkingsfare d,e,f,g: oransje skravur



TK03-07
Intermediær til litt kalkrik fukt-kystlynghei
Kalkinnhold d,e,f: vannrett skravur. Uttørkingsfare d,e,f,g: oransje skravur. Vannmetning b,c: sirkel 1.0 mm




TK03-05
Sterkt kalkrik veldrenert-vekselfuktig kystlynghei
Kalkinnhold g,h,i: loddrett skravur. Uttørkingsfare d,e,f,g: oransje skravur



TK03-08
Sterkt kalkrik fukt-kystlynghei
Kalkinnhold g,h,i: loddrett skravur. Uttørkingsfare d,e,f,g: oransje skravur. Vannmetning b,c: sirkel 1.0 mm

TH01 Avskoget hei og eng

1:50 000 · 2 enheter



TH01-01
Kalkfattig til litt kalkrik avskoget hei og eng
Kalkinnhold b,c,d,e,f: vannrett skravur

1:20 000 · 6 enheter



TH01-01
Kalkfattig avskoget bærlynghei
Kalkinnhold b,c: skrå skravur. Uttørkingsfare b,c: grå skravur



TH01-02
Intermediær til litt kalkrik bærlynghei
Kalkinnhold d,e,f: vannrett skravur. Uttørkingsfare b,c: grå skravur



TH01-04
Kalkfattig avskoget lynghei og -lavhei
Kalkinnhold b,c: skrå skravur. Uttørkingsfare d,e,f,g,h: oransje skravur


1:5 000 · 14 enheter



TH01-01
Kalkfattig avskoget bærlynghei
Kalkinnhold b,c: skrå skravur. Uttørkingsfare b,c: grå skravur



TH01-02
Intermediær til litt kalkrik bærlynghei
Kalkinnhold d,e,f: vannrett skravur. Uttørkingsfare b,c: grå skravur



TH01-10
Avskoget storbregne-fjelleng
Kalkinnhold d,e,f: vannrett skravur. Uttørkingsfare b,c: grå skravur. Vannmetning b,c: sirkel 1.0 mm



TH01-04
Kalkfattig avskoget lynghei
Kalkinnhold b,c: skrå skravur. Uttørkingsfare d,e: oransje skravur



TH01-07
Kalkfattig avskoget lavhei
Kalkinnhold b,c: skrå skravur. Uttørkingsfare f,g,h: mørk rød skravur

1:50 000 · 2 enheter	1:20 000 · 6 enheter	1:5 000 · 14 enheter
		TH01-12 Avskoget kalkfattig fjell-fukthei Kalkinnhold b,c: skrå skravur. Uttørkingsfare d,e: oransje skravur. Vannmetning b,c: sirkel 1.0 mm
	TH01-05 Intermediær til litt kalkrik avskoget lynghei og -lavhei Kalkinnhold d,e,f: vannrett skravur. Uttørkingsfare d,e,f,g,h: oransje skravur	**TH01-05** Intermediær til litt kalkrik avskoget lynghei Kalkinnhold d,e,f: vannrett skravur. Uttørkingsfare d,e: oransje skravur
		TH01-08 Intermediær til litt kalkrik avskoget lavhei Kalkinnhold d,e,f: vannrett skravur. Uttørkingsfare f,g,h: mørk rød skravur
		TH01-13 Avskoget intermediær til svakt kalkfattig fjell-fukthei Kalkinnhold d,e,f: vannrett skravur. Uttørkingsfare d,e: oransje skravur. Vannmetning b,c: sirkel 1.0 mm
TH01-02 Klart kalkrik avskoget hei og eng Kalkinnhold g,h,i: loddrett skravur	**TH01-03** Klart kalkrik avskoget bærlynghei Kalkinnhold g,h,i: loddrett skravur. Uttørkingsfare b,c: grå skravur	**TH01-03** Klart kalkrik avskoget bærlynghei Kalkinnhold g,h,i: loddrett skravur. Uttørkingsfare b,c: grå skravur
		TH01-11 Avskoget høgstaude-fjelleng Kalkinnhold g,h,i: loddrett skravur. Uttørkingsfare b,c: grå skravur. Vannmetning b,c: sirkel 1.0 mm
	TH01-06 Klart kalkrik avskoget lynghei og -lavhei Kalkinnhold g,h,i: loddrett skravur. Uttørkingsfare d,e,f,g,h: oransje skravur	**TH01-06** Klart kalkrik avskoget lynghei Kalkinnhold g,h,i: loddrett skravur. Uttørkingsfare d,e: oransje skravur
		TH01-09 Klart kalkrik avskoget lavhei Kalkinnhold g,h,i: loddrett skravur. Uttørkingsfare f,g,h: mørk rød skravur
		TH01-14 Avskoget kalkrik fjell-fukteng Kalkinnhold g,h,i: loddrett skravur. Uttørkingsfare d,e: oransje skravur. Vannmetning b,c: sirkel 1.0 mm

TO01 Åker

1:50 000 · 1 enheter	1:20 000 · 1 enheter	1:5 000 · 1 enheter
TO01-01 Åker	**TO01-01** Åker	**TO01-01** Åker

TO02 Oppdyrket mark med semi-naturlig engpreg

1:50 000 · 1 enheter



TO02-01
Oppdyrket mark med semi-naturlig engpreg

1:20 000 · 1 enheter



TO02-01
Oppdyrket mark med semi-naturlig engpreg

1:5 000 · 1 enheter



TO02-01
Oppdyrket mark med semi-naturlig engpreg

TO03 Oppdyrket varig eng

1:50 000 · 1 enheter



TO03-01
Oppdyrket varig eng

1:20 000 · 1 enheter



TO03-01
Oppdyrket varig eng

1:5 000 · 4 enheter



TO03-01
Intensivt høstet og ugjødslet til temmelig sterkt gjødslet oppdyrket varig eng



TO03-02
Intensivt høstet og sterkt gjødslet oppdyrket varig eng
Gjødslingsintensitet c: trekant 1.0 mm



TO03-03
Intensivt høstet og overgjødslet oppdyrket varig eng
Høstingsintensitet y: rute 1.0 mm



TO03-04
Svært intensivt høstet og overgjødslet oppdyrket varig eng
Høstingsintensitet y: rute 1.0 mm. Gjødslingsintensitet c: trekant 1.0 mm

TO04 Upløyd jordbruksmark med intensivt hevdpreg

1:50 000 · 1 enheter



TO04-01
Upløyd jordbruksmark med intensivt hevdpreg

1:20 000 · 1 enheter



TO04-01
Upløyd jordbruksmark med intensivt hevdpreg


1:5 000 · 3 enheter



TO04-01
Intensivt høstet jordbruksmark uten markbearbeiding



TO04-02
Intensivt høstet jordbruksmark med utjevnet overflate
Markbearbeidingsintensitet b: rute 1.0 mm



TO04-03
Svært intensivt høstet jordbruksmark med utjevnet overflate
Markbearbeidingsintensitet b: rute 1.0 mm. Skilles fra naboenhet med symbol: vinkel 1.0 mm

TN01 Blomsterbed og annen hyppig bearbeidet mark

1:50 000 · 1 enheter



TN01-01
Blomsterbed og annen hyppig bearbeidet mark

1:20 000 · 1 enheter



TN01-01
Blomsterbed og annen hyppig bearbeidet mark

1:5 000 · 1 enheter



TN01-01
Blomsterbed og annen hyppig bearbeidet mark

TN03 Vegkanter, plener, parker og liknende uten semi-naturlig hevdpreg

1:50 000 · 1 enheter



TN03-01
Vegkanter, plener, parker og liknende uten semi-naturlig hevdpreg

1:20 000 · 1 enheter



TN03-01
Vegkanter, plener, parker og liknende uten semi-naturlig hevdpreg

1:5 000 · 1 enheter



TN03-01
Vegkanter, plener, parker og liknende uten semi-naturlig hevdpreg

TA01 Nakent berg

1:50 000 · 2 enheter



TA01-01
Svært kalkfattig til noe kalkrikt nakent berg

1:20 000 · 8 enheter



TA01-01
Lite uttørkingseksponert svært til noe kalkfattig nakent berg
Kalkinnhold a,b,c,d: skrå skravur. Uttørkingseksponering 0,a,b,c: grå skravur



TA01-02
Uttørkingseksponert svært til noe kalkfattig nakent berg
Kalkinnhold a,b,c,d: skrå skravur

1:5 000 · 23 enheter



TA01-01
Svært lite uttørkingseksponert svært kalkfattig nakent berg
Kalkinnhold a,b: skrå skravur. Uttørkingseksponering 0,a,b,c: grå skravur. Skilles fra naboenhet med prikket skravur



TA01-02
Nokså lite uttørkingseksponert svært kalkfattig nakent berg
Kalkinnhold a,b: skrå skravur. Uttørkingseksponering b,c: grå skravur



TA01-05
Svært lite uttørkingseksponert noe kalkfattig nakent berg
Kalkinnhold c,d: skrå skravur. Uttørkingseksponering 0,a,b,c: grå skravur. Skilles fra naboenhet med prikket skravur. Skilles fra naboenhet med symbol: vinkel 1.0 mm




TA01-06
Nokså lite uttørkingseksponert noe kalkfattig nakent berg
Kalkinnhold c,d: skrå skravur. Uttørkingseksponering b,c: grå skravur. Skilles fra naboenhet med symbol: vinkel 1.0 mm




TA01-03
Nokså uttørkingseksponert svært kalkfattig nakent berg
Kalkinnhold a,b: skrå skravur





TA01-04
Svært uttørkingseksponert svært kalkfattig nakent berg
Kalkinnhold a,b: skrå skravur. Uttørkingseksponering f,g: mørk rød skravur

1:50 000 · 2 enheter	1:20 000 · 8 enheter	1:5 000 · 23 enheter
		 **TA01-07** Nokså uttørkingseksponert noe kalkfattig nakent berg Kalkinnhold c,d: skrå skravur. Skilles fra naboenhet med prikket skravur
		 **TA01-08** Svært uttørkingseksponert noe kalkfattig nakent berg Kalkinnhold c,d: skrå skravur. Uttørkingseksponering f,g: mørk rød skravur. Skilles fra naboenhet med prikket skravur
	 **TA01-03** Lite uttørkingseksponert noe kalkrikt nakent berg Kalkinnhold e,f: vannrett skravur. Uttørkingseksponering 0,a,b,c: grå skravur	 **TA01-09** Svært lite uttørkingseksponert noe kalkrikt nakent berg Kalkinnhold e,f: vannrett skravur. Uttørkingseksponering 0,a,b,c: grå skravur. Skilles fra naboenhet med prikket skravur
		 **TA01-10** Nokså lite uttørkingseksponert noe kalkrikt nakent berg Kalkinnhold e,f: vannrett skravur. Uttørkingseksponering b,c: grå skravur
	 **TA01-04** Uttørkingseksponert noe kalkrikt nakent berg Kalkinnhold e,f: vannrett skravur	 **TA01-11** Nokså uttørkingseksponert noe kalkrikt nakent berg Kalkinnhold e,f: vannrett skravur
		 **TA01-12** Svært uttørkingseksponert noe kalkrikt nakent berg Kalkinnhold e,f: vannrett skravur. Uttørkingseksponering f,g: mørk rød skravur
	 **TA01-07** Kalkfattig snøleieberg Kalkinnhold a,b,c,d: skrå skravur. Snødekkebetinget vekstsesongreduksjon a,b,c,d,e,f: sirkel 1.0 mm	 **TA01-21** Kalkfattig snøleieberg Kalkinnhold a,b,c,d: skrå skravur. Snødekkebetinget vekstsesongreduksjon a,b,c,d,e,f: sirkel 1.0 mm
	 **TA01-08** Kalkrikt snøleieberg Kalkinnhold e,f,g,h,i: loddrett skravur. Snødekkebetinget vekstsesongreduksjon a,b,c,d,e,f: sirkel 1.0 mm	 **TA01-22** Kalkrikt snøleieberg Kalkinnhold e,f,g,h,i: loddrett skravur. Snødekkebetinget vekstsesongreduksjon a,b,c,d,e,f: sirkel 1.0 mm
 **TA01-02** Kalkrikt nakent berg Kalkinnhold g,h,i: loddrett skravur	 **TA01-05** Lite uttørkingseksponert kalkrikt nakent berg Kalkinnhold g,h,i: loddrett skravur. Uttørkingseksponering 0,a,b,c: grå skravur	 **TA01-13** Svært lite uttørkingseksponert klart kalkrikt nakent berg Kalkinnhold g,h: loddrett skravur. Uttørkingseksponering 0,a: blå skravur
		 **TA01-14** Nokså lite uttørkingseksponert klart kalkrikt nakent berg Kalkinnhold g,h: loddrett skravur. Uttørkingseksponering b,c: grå skravur
		 **TA01-17** Svært lite uttørkingseksponert ekstremt kalkrikt nakent berg Kalkinnhold g,h,i: loddrett skravur. Uttørkingseksponering 0,a,b,c: grå skravur. Skilles fra naboenhet med prikket skravur
		 **TA01-18** Nokså lite uttørkingseksponert ekstremt kalkrikt nakent berg Kalkinnhold i: loddrett skravur. Uttørkingseksponering b,c: grå skravur. Skilles fra naboenhet med symbol: vinkel 1.0 mm

1:50 000 · 2 enheter	1:20 000 · 8 enheter	1:5 000 · 23 enheter
	 **TA01-06** Uttørkingseksponert kalkrikt nakent berg Kalkinnhold g,h,i: loddrett skravur	 **TA01-15** Nokså uttørkingseksponert klart kalkrikt nakent berg Kalkinnhold g,h: loddrett skravur. Uttørkingseksponering d,e: oransje skravur
		 **TA01-16** Svært uttørkingseksponert klart kalkrikt nakent berg Kalkinnhold g,h: loddrett skravur. Uttørkingseksponering f,g: mørk rød skravur
		 **TA01-19** Nokså uttørkingseksponert ekstremt kalkrikt nakent berg Kalkinnhold g,h,i: loddrett skravur
		 **TA01-20** Svært uttørkingseksponert ekstremt kalkrikt nakent berg Kalkinnhold g,h,i: loddrett skravur. Uttørkingseksponering f,g: mørk rød skravur. Skilles fra naboenhet med prikket skravur
Ingen enhet i katalogen	Ingen enhet i katalogen	 **TA01-23** Fuglestein og fugleberg Naturlig gjødsling b,c,d,y: trekant 1.0 mm

TA02 Åpen grunnlendt mark

1:50 000 · 2 enheter	1:20 000 · 3 enheter	1:5 000 · 9 enheter
 **TA02-01** Kalkfattig til litt kalkrik åpen grunnlendt mark Kalkinnhold b,c,d,e,f: vannrett skravur	 **TA02-01** Kalkfattig åpen grunnlendt mark Kalkinnhold b,c: skrå skravur	 **TA02-01** Kalkfattig åpen grunnlendt lyngmark Kalkinnhold b,c: skrå skravur. Uttørkingsfare e,f: oransje skravur
		 **TA02-04** Kalkfattig åpen grunnlendt lavmark Kalkinnhold b,c: skrå skravur. Uttørkingsfare g,h: mørk rød skravur
		 **TA02-07** Kalkfattig grunnlendt åpen fukt-lyngmark Kalkinnhold b,c: skrå skravur. Uttørkingsfare e,f: oransje skravur. Vannmetning b,c: sirkel 1.0 mm
	 **TA02-02** Intermediær til litt kalkrik åpen grunnlendt mark Kalkinnhold d,e,f: vannrett skravur	 **TA02-02** Intermediær til litt kalkrik åpen grunnlendt lyngmark Kalkinnhold d,e,f: vannrett skravur. Uttørkingsfare e,f: oransje skravur
		 **TA02-05** Intermediær til litt kalkrik åpen grunnlendt lavmark Kalkinnhold d,e,f: vannrett skravur. Uttørkingsfare g,h: mørk rød skravur
		 **TA02-08** Intermediær til litt kalkrik grunnlendt åpen fukt-lyngmark Kalkinnhold d,e,f: vannrett skravur. Uttørkingsfare e,f: oransje skravur. Vannmetning b,c: sirkel 1.0 mm

1:50 000 · 2 enheter



TA02-02
Temmelig til ekstremt kalkrik åpen grunnlendt mark
Kalkinnhold g,h,i: loddrett skravur

1:20 000 · 3 enheter



TA02-03
Temmelig til ekstremt kalkrik åpen grunnlendt mark
Kalkinnhold g,h,i: loddrett skravur

1:5 000 · 9 enheter



TA02-03
Temmelig til ekstremt kalkrik åpen grunnlendt lyngmark
Kalkinnhold g,h,i: loddrett skravur. Uttørkingsfare e,f: oransje skravur



TA02-06
Temmelig til ekstremt kalkrik åpen grunnlendt lavmark
Kalkinnhold g,h,i: loddrett skravur. Uttørkingsfare g,h: mørk rød skravur



TA02-09
Temmelig til ekstremt kalkrik grunnlendt åpen fukt-lyngmark
Kalkinnhold g,h,i: loddrett skravur. Uttørkingsfare e,f: oransje skravur. Vannmetning b,c: sirkel 1.0 mm

TC01 Strandberg

1:50 000 · 1 enheter



TC01-01
Strandberg

1:20 000 · 2 enheter




TC01-01
Kalkfattig til litt kalkrikt strandberg
Kalkinnhold b,c,d,e,f: vannrett skravur




TC01-02
Sterkt kalkrikt strandberg
Kalkinnhold g,h,i: loddrett skravur

1:5 000 · 3 enheter



TC01-01
Kalkfattig til litt kalkrikt beskyttet til litt eksponert strandberg
Kalkinnhold b,c,d,e,f: vannrett skravur



TC01-03
Temmelig til ekstremt eksponert strandberg
Kalkinnhold b,c,d,e,f: vannrett skravur. Vannforstyrrelsesintensitet f,g,h,y: kryss 1.0 mm



TC01-02
Sterkt kalkrikt strandberg
Kalkinnhold g,h,i: loddrett skravur

TC02 Grotte og overheng

1:50 000 · 2 enheter




TC02-01
Kalkfattig til litt kalkrik grotte og overheng
Kalkinnhold a,b,c,d,e,f: skrå skravur. Grottebetinget skjerming a,b,c,d: vinkel 1.6 mm


1:20 000 · 6 enheter



TC02-01
Knapt uttørkingseksponert kalkfattig grotte og overheng
Kalkinnhold a,b,c: skrå skravur. Uttørkingseksponering 0,a,b,c: grå skravur. Grottebetinget skjerming a: vinkel 1.0 mm



TC02-02
Knapt uttørkingseksponert intermediært til litt kalkrik grotte og overheng
Kalkinnhold d,e,f: vannrett skravur. Uttørkingseksponering 0,a,b,c: grå skravur. Grottebetinget skjerming a: vinkel 1.0 mm



TC02-04
Uttørkingseksponert kalkfattig overheng
Kalkinnhold a,b,c: skrå skravur. Uttørkingseksponering d,e,f,g: mørk rød skravur. Grottebetinget skjerming a: vinkel 1.0 mm

1:5 000 · 8 enheter








TC02-01
Knapt uttørkingseksponert kalkfattig overheng
Kalkinnhold a,b,c: skrå skravur. Uttørkingseksponering 0,a,b,c: grå skravur. Grottebetinget skjerming a: vinkel 1.0 mm






TC02-02
Knapt uttørkingseksponert intermediært og litt kalkrikt overheng
Kalkinnhold d,e,f: vannrett skravur. Uttørkingseksponering 0,a,b,c: grå skravur. Grottebetinget skjerming a: vinkel 1.0 mm













TC02-06
Uttørkingseksponert kalkfattig overheng
Kalkinnhold a,b,c: skrå skravur. Uttørkingseksponering d,e,f,g: mørk rød skravur. Grottebetinget skjerming a: vinkel 1.0 mm









1:50 000 · 2 enheter	1:20 000 · 6 enheter	1:5 000 · 8 enheter
	 **TC02-05** Uttørkingseksponert intermediært til litt kalkrikt overheng Kalkinnhold d,e,f: vannrett skravur. Uttørkingseksponering d,e,f,g: mørk rød skravur. Grottebetinget skjerming a: vinkel 1.0 mm	 **TC02-07** Uttørkingseksponert intermediært og litt kalkrikt overheng Kalkinnhold d,e,f: vannrett skravur. Uttørkingseksponering d,e,f,g: mørk rød skravur. Grottebetinget skjerming a: vinkel 1.0 mm
 **TC02-02** Sterkt kalkrik grotte og overheng Grottebetinget skjerming a,b,c,d,y: vinkel 1.0 mm	 **TC02-03** Knapt uttørkingseksponert sterkt kalkrik grotte og overheng Uttørkingseksponering 0,a,b,c: grå skravur. Grottebetinget skjerming a,b,c,d,y: vinkel 1.0 mm	 **TC02-03** Knapt uttørkingseksponert sterkt kalkrikt overheng Kalkinnhold g,h,i: loddrett skravur. Uttørkingseksponering 0,a,b,c: grå skravur. Grottebetinget skjerming a: vinkel 1.0 mm
		 **TC02-05** Kalkgrotte Uttørkingseksponering 0: blå skravur. Grottebetinget skjerming b,c,d,y: vinkel 1.6 mm
	 **TC02-06** Uttørkingseksponert sterkt kalkrikt overheng Kalkinnhold g,h,i: loddrett skravur. Uttørkingseksponering d,e,f,g: mørk rød skravur. Grottebetinget skjerming a: vinkel 1.0 mm	 **TC02-08** Uttørkingseksponert sterkt kalkrikt overheng Kalkinnhold g,h,i: loddrett skravur. Uttørkingseksponering d,e,f,g: mørk rød skravur. Grottebetinget skjerming a: vinkel 1.0 mm
Ingen enhet i katalogen	Ingen enhet i katalogen	 **TC02-04** Kalkfattig til litt kalkrik grotte Kalkinnhold a,b,c,d,e,f: skrå skravur. Uttørkingseksponering 0: blå skravur. Grottebetinget skjerming b,c,d: vinkel 2.2 mm

TG01 Nakne løsmasser

1:50 000 · 12 enheter	1:20 000 · 19 enheter	1:5 000 · 41 enheter
 **TG01-01** Fjellnatur-pregede kalkfattige til svakt kalkrike stedegne grus-løsmasser, stein og blokkmark Stedegne løsmasser: egen nyanse av fyllfargen. Dominerende kornstørrelse D,E,F: firkant 2.2 mm	 **TG01-01** Udifferensierte stedegne grus-løsmasser Stedegne løsmasser: egen nyanse av fyllfargen. Dominerende kornstørrelse D: firkant 1.0 mm	 **TG01-01** Udifferensierte stedegne grus-løsmasser Stedegne løsmasser: egen nyanse av fyllfargen. Dominerende kornstørrelse D: firkant 1.0 mm
	 **TG01-02** Fjellhei-, leside- eller grasmarkspregede kalkfattige stedegne grus-løsmasser Stedegne løsmasser: egen nyanse av fyllfargen. Kalkinnhold a,b,c: skrå skravur. Økologisk differensiering B: sirkel 1.6 mm. Dominerende kornstørrelse D: firkant 1.0 mm	 **TG01-04** Fjellhei-, leside- eller grasmarkspregede kalkfattige stedegne grus-løsmasser Stedegne løsmasser: egen nyanse av fyllfargen. Kalkinnhold a,b,c: skrå skravur. Økologisk differensiering B: sirkel 1.6 mm. Dominerende kornstørrelse D: firkant 1.0 mm
	 **TG01-03** Fjellhei-, leside- eller grasmarkspregede intermediære til svakt kalkrike stedegne grus-løsmasser Stedegne løsmasser: egen nyanse av fyllfargen. Kalkinnhold a,b,c,d,e,f: skrå skravur. Økologisk differensiering A,B,C: sirkel 1.6 mm. Dominerende kornstørrelse D: firkant 1.0 mm. Skilles fra naboenhet med prikket skravur	 **TG01-02** Rabbepregede kalkfattige til svakt kalkrike stedegne grus-løsmasser Stedegne løsmasser: egen nyanse av fyllfargen. Kalkinnhold a,b,c,d,e,f: skrå skravur. Økologisk differensiering A: sirkel 1.6 mm. Dominerende kornstørrelse D: firkant 1.0 mm

1:50 000 · 12 enheter	1:20 000 · 19 enheter	1:5 000 · 41 enheter
		 **TG01-05** Fjellhei-, leside- eller grasmarkspregede intermediære til svakt kalkrike stedegne grus-løsmasser Stedegne løsmasser: egen nyanse av fyllfargen. Kalkinnhold d,e,f: vannrett skravur. Økologisk differensiering B: sirkel 1.6 mm. Dominerende kornstørrelse D: firkant 1.0 mm
		 **TG01-07** Snøleiepregede kalkfattige til svakt kalkrike stedegne grus-løsmasser Stedegne løsmasser: egen nyanse av fyllfargen. Kalkinnhold a,b,c,d,e,f: skrå skravur. Økologisk differensiering C: sirkel 1.6 mm. Dominerende kornstørrelse D: firkant 1.0 mm
	 **TG01-05** Udifferensiert stedegen stein- og blokkmark Stedegne løsmasser: egen nyanse av fyllfargen	 **TG01-09** Udifferensiert stedegen stein- og blokkmark Stedegne løsmasser: egen nyanse av fyllfargen
	 **TG01-06** Rabbe- og snøleiepreget kalkfattig til svakt kalkrik stedegen stein- og blokkmark Stedegne løsmasser: egen nyanse av fyllfargen. Kalkinnhold a,b,c,d,e,f: skrå skravur. Økologisk differensiering A,C: sirkel 1.6 mm	 **TG01-10** Rabbepreget kalkfattig til svakt kalkrik stedegen stein- og blokkmark Stedegne løsmasser: egen nyanse av fyllfargen. Kalkinnhold a,b,c,d,e,f: skrå skravur. Økologisk differensiering A: sirkel 1.6 mm
		 **TG01-12** Snøleiepreget kalkfattig til svakt kalkrik stedegen stein- og blokkmark Stedegne løsmasser: egen nyanse av fyllfargen. Kalkinnhold a,b,c,d,e,f: skrå skravur. Økologisk differensiering C: sirkel 1.6 mm
 **TG01-02** Fjellnatur-pregede sterkt kalkrike stedegne grus-løsmasser, stein og blokkmark Stedegne løsmasser: egen nyanse av fyllfargen. Kalkinnhold g,h,i: loddrett skravur. Økologisk differensiering A,B,C: sirkel 1.6 mm. Dominerende kornstørrelse D,E,F: firkant 2.2 mm	 **TG01-04** Fjellnatur-pregede sterkt kalkrike stedegne grus-løsmasser Stedegne løsmasser: egen nyanse av fyllfargen. Kalkinnhold g,h,i: loddrett skravur. Økologisk differensiering A,B,C: sirkel 1.6 mm. Dominerende kornstørrelse D: firkant 1.0 mm	 **TG01-03** Rabbepregede sterkt kalkrike stedegne grus-løsmasser Stedegne løsmasser: egen nyanse av fyllfargen. Kalkinnhold g,h,i: loddrett skravur. Økologisk differensiering A: sirkel 1.6 mm. Dominerende kornstørrelse D: firkant 1.0 mm
		 **TG01-06** Fjellhei-, leside- eller grasmarkspregede sterkt kalkrike stedegne grus-løsmasser Stedegne løsmasser: egen nyanse av fyllfargen. Kalkinnhold g,h,i: loddrett skravur. Økologisk differensiering B: sirkel 1.6 mm. Dominerende kornstørrelse D: firkant 1.0 mm
		 **TG01-08** Snøleiepregede sterkt kalkrike stedegne grus-løsmasser Stedegne løsmasser: egen nyanse av fyllfargen. Kalkinnhold g,h,i: loddrett skravur. Økologisk differensiering C: sirkel 1.6 mm. Dominerende kornstørrelse D: firkant 1.0 mm
	 **TG01-07** Rabbe- og snøleiepreget sterkt kalkrik stedegen stein- og blokkmark Stedegne løsmasser: egen nyanse av fyllfargen. Kalkinnhold g,h,i: loddrett skravur. Økologisk differensiering A,C: sirkel 1.6 mm	 **TG01-11** Rabbepreget sterkt kalkrik stedegen stein- og blokkmark Stedegne løsmasser: egen nyanse av fyllfargen. Kalkinnhold g,h,i: loddrett skravur. Økologisk differensiering A: sirkel 1.6 mm

1:50 000 · 12 enheter	1:20 000 · 19 enheter	1:5 000 · 41 enheter
		 **TG01-13** Snøleiepreget sterkt kalkrik stedegen stein- og blokkmark Stedegne løsmasser: egen nyanse av fyllfargen. Kalkinnhold g,h,i: loddrett skravur. Økologisk differensiering C: sirkel 1.6 mm
 **TG01-03** Moreneblokkmark Morene: egen nyanse av fyllfargen. Dominerende kornstørrelse D,E,F: firkant 2.2 mm	 **TG01-08** Moreneblokkmark Morene: egen nyanse av fyllfargen. Dominerende kornstørrelse D,E,F: firkant 2.2 mm	 **TG01-14** Udifferensiert moreneblokkmark Morene: egen nyanse av fyllfargen. Dominerende kornstørrelse D,E,F: firkant 2.2 mm
		 **TG01-15** Fjellnatur-preget moreneblokkmark Morene: egen nyanse av fyllfargen. Økologisk differensiering A,B,C: sirkel 1.6 mm. Dominerende kornstørrelse D,E,F: firkant 2.2 mm
		 **TG01-16** Skogsmarkspreget moreneblokkmark Morene: egen nyanse av fyllfargen. Økologisk differensiering D: sirkel 1.6 mm. Dominerende kornstørrelse D,E,F: firkant 2.2 mm
 **TG01-04** Hevet grus-, stein- og blokkstrand Hevet strand: egen nyanse av fyllfargen. Dominerende kornstørrelse D,E,F: firkant 2.2 mm	 **TG01-09** Udifferensiert hevet grus-, stein- og blokkstrand Hevet strand: egen nyanse av fyllfargen. Dominerende kornstørrelse D,E,F: firkant 2.2 mm	 **TG01-17** Udifferensiert hevet grusstrand Hevet strand: egen nyanse av fyllfargen. Dominerende kornstørrelse D: firkant 1.0 mm
		 **TG01-21** Udifferensiert hevet stein- og blokkstrand Hevet strand: egen nyanse av fyllfargen
	 **TG01-10** Rabbe- og grasmarkspreget hevet grus-, stein- og blokkstrand Hevet strand: egen nyanse av fyllfargen. Økologisk differensiering A,B: sirkel 1.6 mm. Dominerende kornstørrelse D,E,F: firkant 2.2 mm	 **TG01-18** Rabbepreget hevet grusstrand Hevet strand: egen nyanse av fyllfargen. Økologisk differensiering A: sirkel 1.6 mm. Dominerende kornstørrelse D: firkant 1.0 mm
		 **TG01-19** Grasmarkspreget hevet grusstrand Hevet strand: egen nyanse av fyllfargen. Økologisk differensiering B: sirkel 1.6 mm. Dominerende kornstørrelse D: firkant 1.0 mm
		 **TG01-22** Rabbepreget hevet stein- og blokkstrand Hevet strand: egen nyanse av fyllfargen. Økologisk differensiering A: sirkel 1.6 mm
		 **TG01-23** Grasmarkspreget hevet stein- og blokkstrand Hevet strand: egen nyanse av fyllfargen. Økologisk differensiering B: sirkel 1.6 mm
	 **TG01-11** Skogsmarkspreget hevet grus-, stein- og blokkstrand Hevet strand: egen nyanse av fyllfargen. Økologisk differensiering D: sirkel 1.6 mm. Dominerende kornstørrelse D,E,F: firkant 2.2 mm	 **TG01-20** Skogsmarkspreget hevet grusstrand Hevet strand: egen nyanse av fyllfargen. Økologisk differensiering D: sirkel 1.6 mm. Dominerende kornstørrelse D: firkant 1.0 mm


1:50 000 · 12 enheter	1:20 000 · 19 enheter	1:5 000 · 41 enheter
		 **TG01-24** Skogsmarkspreget hevet stein- og blokkstrand Hevet strand: egen nyanse av fyllfargen. Økologisk differensiering D: sirkel 1.6 mm
 **TG01-05** Breforland og snøavsmeltingsområde Breforland og snøavsmeltingsområde: egen nyanse av fyllfargen. Dominerende kornstørrelse A,B,C,D,E,F,G: firkant 1.6 mm	 **TG01-12** Breforland og snøavsmeltingsområde Breforland og snøavsmeltingsområde: egen nyanse av fyllfargen. Dominerende kornstørrelse A,B,C,D,E,F,G: firkant 1.6 mm	 **TG01-25** Udifferensiert leire-, silt-, sand og grusdominert breforland og snøavsmeltingsområde Breforland og snøavsmeltingsområde: egen nyanse av fyllfargen. Dominerende kornstørrelse A,B,C,D: firkant 1.6 mm
		 **TG01-26** Fjellnatur-preget leire-, silt-, sand og grusdominert breforland og snøavsmeltingsområde Breforland og snøavsmeltingsområde: egen nyanse av fyllfargen. Økologisk differensiering A,B,C: sirkel 1.6 mm. Dominerende kornstørrelse A,B,C,D: firkant 1.6 mm
		 **TG01-27** Skogsmarkspreget leire-, silt-, sand og grusdominert breforland og snøavsmeltingsområde Breforland og snøavsmeltingsområde: egen nyanse av fyllfargen. Økologisk differensiering D: sirkel 1.6 mm. Dominerende kornstørrelse A,B,C,D: firkant 1.6 mm
		 **TG01-28** Udifferensiert breforland og snøavsmeltingsområde dominert av stein og blokk Breforland og snøavsmeltingsområde: egen nyanse av fyllfargen
		 **TG01-29** Fjellnatur-preget breforland og snøavsmeltingsområde dominert av stein og blokk Breforland og snøavsmeltingsområde: egen nyanse av fyllfargen. Økologisk differensiering A,B,C: sirkel 1.6 mm
 **TG01-06** Konsoliderte marine bresedimenter Konsoliderte marine bresedimenter: egen nyanse av fyllfargen. Kalkinnhold d,e,f,g,h,i: vannrett skravur. Dominerende kornstørrelse D,E,F: firkant 2.2 mm	 **TG01-13** Konsoliderte marine bresedimenter Konsoliderte marine bresedimenter: egen nyanse av fyllfargen. Kalkinnhold d,e,f,g,h,i: vannrett skravur. Dominerende kornstørrelse D,E,F: firkant 2.2 mm	 **TG01-30** Konsoliderte marine bresedimenter Konsoliderte marine bresedimenter: egen nyanse av fyllfargen. Kalkinnhold d,e,f,g,h,i: vannrett skravur. Dominerende kornstørrelse D,E,F: firkant 2.2 mm
 **TG01-07** Historisk silt- og leirskred Historisk skred: egen nyanse av fyllfargen. Kalkinnhold e,f,g,h: vannrett skravur. Dominerende kornstørrelse A,B: firkant 1.0 mm	 **TG01-14** Historisk silt- og leirskred Historisk skred: egen nyanse av fyllfargen. Kalkinnhold e,f,g,h: vannrett skravur. Dominerende kornstørrelse A,B: firkant 1.0 mm	 **TG01-31** Udifferensiert historisk silt- og leirskred Historisk skred: egen nyanse av fyllfargen. Kalkinnhold e,f,g,h: vannrett skravur. Dominerende kornstørrelse A,B: firkant 1.0 mm
		 **TG01-32** Skogsmarkspreget historisk silt- og leirskred Historisk skred: egen nyanse av fyllfargen. Kalkinnhold e,f,g,h: vannrett skravur. Økologisk differensiering D: sirkel 1.6 mm. Dominerende kornstørrelse A,B: firkant 1.0 mm
 **TG01-08** Historisk skred av sand og grus Historisk skred: egen nyanse av fyllfargen. Dominerende kornstørrelse C,D: firkant 2.2 mm	 **TG01-15** Historisk skred av sand og grus Historisk skred: egen nyanse av fyllfargen. Dominerende kornstørrelse C,D: firkant 2.2 mm	 **TG01-33** Udifferensiert historisk skred av sand og grus Historisk skred: egen nyanse av fyllfargen. Dominerende kornstørrelse C,D: firkant 2.2 mm

1:50 000 · 12 enheter	1:20 000 · 19 enheter	1:5 000 · 41 enheter
		TG01-34 Skogsmarkspreget historisk skred av sand og grus Historisk skred: egen nyanse av fyllfargen. Økologisk differensiering D: sirkel 1.6 mm. Dominerende kornstørrelse C,D: firkant 2.2 mm
TG01-09 Historisk steinskred Historisk skred: egen nyanse av fyllfargen. Skilles fra naboenhet med symbol: stjerne 1.0 mm	**TG01-16** Historisk steinskred Historisk skred: egen nyanse av fyllfargen. Skilles fra naboenhet med symbol: stjerne 1.0 mm	**TG01-35** Historisk steinskred Historisk skred: egen nyanse av fyllfargen. Skilles fra naboenhet med symbol: stjerne 1.0 mm
		TG01-36 Skogsmarkspreget historisk steinskred Historisk skred: egen nyanse av fyllfargen. Økologisk differensiering D: sirkel 1.6 mm. Skilles fra naboenhet med symbol: stjerne 1.0 mm
TG01-10 Historisk jordskred Historisk skred: egen nyanse av fyllfargen	**TG01-17** Historisk jordskred Historisk skred: egen nyanse av fyllfargen	**TG01-37** Historisk jordskred Historisk skred: egen nyanse av fyllfargen
		TG01-38 Snøleiepreget historisk jordskred Historisk skred: egen nyanse av fyllfargen. Økologisk differensiering C: sirkel 1.6 mm
		TG01-39 Skogsmarkspreget historisk jordskred Historisk skred: egen nyanse av fyllfargen. Økologisk differensiering D: sirkel 1.6 mm
TG01-11 Synkehull i permafrost Historisk skred: egen nyanse av fyllfargen. Permafrost A: vinkel 1.0 mm	**TG01-18** Synkehull i permafrost Historisk skred: egen nyanse av fyllfargen. Permafrost A: vinkel 1.0 mm	**TG01-40** Synkehull i permafrost Historisk skred: egen nyanse av fyllfargen. Permafrost A: vinkel 1.0 mm
TG01-12 Flomskredmateriale Flomskredmateriale: egen nyanse av fyllfargen	**TG01-19** Flomskredmateriale Flomskredmateriale: egen nyanse av fyllfargen	**TG01-41** Flomskredmateriale Flomskredmateriale: egen nyanse av fyllfargen

TC03 Løsmasse-strand

1:50 000 · 3 enheter	1:20 000 · 5 enheter	1:5 000 · 6 enheter
TC03-01 Leire- og siltstrand i geolittoral Tørrleggingsvarighet c,d,e,f,g,h: oransje skravur. Dominerende kornstørrelse A,B: firkant 1.6 mm	**TC03-01** Leirestrand i geolittoral Tørrleggingsvarighet c,d,e,f,g,h: oransje skravur. Dominerende kornstørrelse A: firkant 1.0 mm	**TC03-01** Leirestrand i geolittoral Tørrleggingsvarighet c,d,e,f,g,h: oransje skravur. Dominerende kornstørrelse A: firkant 1.0 mm
	TC03-02 Siltstrand i geolittoral Tørrleggingsvarighet c,d,e,f,g,h: oransje skravur. Dominerende kornstørrelse B: firkant 2.2 mm	**TC03-02** Siltstrand i geolittoral Tørrleggingsvarighet c,d,e,f,g,h: oransje skravur. Dominerende kornstørrelse B: firkant 2.2 mm

1:50 000 · 3 enheter



TC03-02
Sand-, skjellsand-, grus-, og ruglebunn-strand i geo- til supralittoral
Dominerende kornstørrelse C,D: firkant 1.0 mm



TC03-03
Stein- og blokkstrand i geo- til supralittoral
Dominerende kornstørrelse A,B,C,D,E,F,G: firkant 2.2 mm

1:20 000 · 5 enheter



TC03-03
Sand-, skjellsand-, grus-, og ruglebunn-strand i geo- til supralittoral
Dominerende kornstørrelse C,D: firkant 1.0 mm




TC03-04
Stein- til blokkstrand i geo- til supralittoral
Dominerende kornstørrelse A,B,C,D,E,F: firkant 1.6 mm



TC03-05
Storblokket strand i geo- til supralittoral

1:5 000 · 6 enheter



TC03-03
Sand- til grus-strand i geo-til supralittoral
Dominerende kornstørrelse C,D: firkant 1.0 mm



TC03-06
Skjellsand- og ruglbunn-strand
Tørrleggingsvarighet c,d,e,f,g,h: oransje skravur. Dominerende kornstørrelse C,D: firkant 1.0 mm




TC03-04
Stein- til blokkstrand i geo- til supralittoral
Dominerende kornstørrelse A,B,C,D,E,F: firkant 1.6 mm



TC03-05
Storblokket strand i geo- til supralittoral

TE01 Sanddynemark

1:50 000 · 2 enheter




TE01-01
Kyst-sanddynemark
Vindutsatthet a,b,c,y: strek 1.6 mm



TE01-02
Innlands-sanddynemark
Vindutsatthet a,b,c: strek 1.0 mm

1:20 000 · 4 enheter




TE01-01
Embryonal- primær- og hvit dyne
Marin salinitet a,b,c,d,e,f,g: plusstegn 1.0 mm. Vindutsatthet a,b,c: strek 1.0 mm



TE01-02
Grå og brun dyne
Vindutsatthet a,b,c,y: strek 1.6 mm. Sandstabilisering d,e,f,g,h,i: stjerne 2.2 mm




TE01-03
Primær og hvit innlandsdyne
Vindutsatthet a,b,c: strek 1.0 mm




TE01-04
Grå og brun innlandsdyne
Vindutsatthet a,b,c: strek 1.0 mm. Sandstabilisering e,f,g,h: stjerne 1.6 mm

1:5 000 · 6 enheter




TE01-01
Embryonal- primær- og hvit dyne
Marin salinitet a,b,c,d,e,f,g: plusstegn 1.0 mm. Vindutsatthet a,b,c: strek 1.0 mm



TE01-02
Grå dyne
Marin salinitet a,b,c,d,e,f,g: plusstegn 1.0 mm. Vindutsatthet a,b,c: strek 1.0 mm. Sandstabilisering e,f: stjerne 1.0 mm



TE01-03
Brun dyne
Vindutsatthet a,b,c,y: strek 1.6 mm. Sandstabilisering d,e,f,g,h,i: stjerne 2.2 mm



TE01-06
Dynetrau
Vannmetning b,c: sirkel 1.0 mm. Vindutsatthet a,b,c: strek 1.0 mm. Sandstabilisering g,h,i: stjerne 1.0 mm



TE01-04
Primær og hvit innlandsdyne
Vindutsatthet a,b,c: strek 1.0 mm



TE01-05
Grå og brun innlandsdyne
Vindutsatthet a,b,c: strek 1.0 mm. Sandstabilisering e,f,g,h: stjerne 1.6 mm

TC04 Saltanrikningsmark

1:50 000 · 1 enheter

TC04-01
Saltanrikningsmark

1:20 000 · 1 enheter

TC04-01
Saltanrikningsmark

1:5 000 · 1 enheter

TC04-01
Saltanrikningsmark

TE06 Marin driftvoll


1:50 000 · 1 enheter

TE06-01
Marin driftvoll


1:20 000 · 1 enheter

TE06-01
Marin driftvoll

1:5 000 · 3 enheter



TE06-01
Beskyttet til litt eksponert marin driftvoll
Vannforstyrrelsesintensitet c,d,e: kryss 1.0 mm. Marin salinitet f,g,h: plusstegn 2.2 mm



TE06-02
Svært til ekstremt eksponert marin driftvoll
Marin salinitet f,g,h: plusstegn 2.2 mm



TE06-03
Brakkvannsdriftvoll
Vannforstyrrelsesintensitet c,d,e,f: kryss 1.6 mm. Marin salinitet b,c,d,e: plusstegn 1.0 mm

TE07 Ferskvannsdriftvoll

1:50 000 · 1 enheter

TE07-01
Ferskvannsdriftvoll

1:20 000 · 1 enheter

TE07-01
Ferskvannsdriftvoll

1:5 000 · 1 enheter

TE07-01
Ferskvannsdriftvoll


TE03 Åpen flomfastmark

Gjelder alle enheter: Blå skravur: flompåvirket.

1:50 000 · 1 enheter

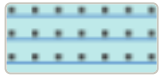
TE03-01
Åpen flomfastmark
Blå skravur: flompåvirket

1:20 000 · 3 enheter




TE03-01
Intermediær til sterkt kalkrik åpen leire- til grus-flomfastmark
Kalkinnhold d,e,f,g,h: vannrett skravur. Blå skravur: flompåvirket. Dominerende kornstørrelse A,B,C,D: firkant 1.6 mm



1:5 000 · 4 enheter



TE03-01
Intermediær til sterkt kalkrik åpen leire- og silt-flomfastmark
Kalkinnhold d,e,f,g,h: vannrett skravur. Blå skravur: flompåvirket. Dominerende kornstørrelse A,B: firkant 1.0 mm



TE03-02
Intermediær til sterkt kalkrik åpen sand- og grus-flomfastmark
Kalkinnhold d,e,f,g,h: vannrett skravur. Blå skravur: flompåvirket. Dominerende kornstørrelse C,D: firkant 2.2 mm



1:50 000 · 1 enheter	1:20 000 · 3 enheter	1:5 000 · 4 enheter
	 **TE03-02** Intermediær til litt kalkrik åpen stein- og blokk-flomfastmark Kalkinnhold d,e,f,g,h: vannrett skravur. Blå skravur: flompåvirket. Dominerende kornstørrelse E,F,G: firkant 2.2 mm	 **TE03-03** Intermediær til litt kalkrik åpen stein- og blokk-flomfastmark Kalkinnhold d,e,f,g,h: vannrett skravur. Blå skravur: flompåvirket. Dominerende kornstørrelse E,F,G: firkant 2.2 mm
	 **TE03-03** Sterkt kalkrik åpen stein- og blokk-flomfastmark Kalkinnhold g,h: loddrett skravur. Blå skravur: flompåvirket. Dominerende kornstørrelse E,F: firkant 1.6 mm	 **TE03-04** Sterkt kalkrik åpen stein- og blokk-flomfastmark Kalkinnhold g,h: loddrett skravur. Blå skravur: flompåvirket. Dominerende kornstørrelse E,F: firkant 1.6 mm

TE04 Langvarig oversvømt flommark

Gjelder alle enheter: Blå skravur: flompåvirket.

1:50 000 · 1 enheter	1:20 000 · 1 enheter	1:5 000 · 1 enheter
 **TE04-01** Langvarig oversvømt flommark Blå skravur: flompåvirket	 **TE04-01** Langvarig oversvømt flommark Blå skravur: flompåvirket	 **TE04-01** Langvarig oversvømt flommark Blå skravur: flompåvirket

TD01 Rasmark

1:50 000 · 2 enheter	1:20 000 · 9 enheter	1:5 000 · 12 enheter
 **TD01-01** Kalkfattig til litt kalkrik rasmark Kalkinnhold b,c,d,e,f: vannrett skravur	 **TD01-01** Kalkfattig sand- og grus-rasmark Kalkinnhold b,c: skrå skravur. Dominerende kornstørrelse C,D: firkant 1.0 mm	 **TD01-01** Kalkfattig sand- og grus-rasmark Kalkinnhold b,c: skrå skravur. Dominerende kornstørrelse C,D: firkant 1.0 mm
	 **TD01-02** Intermediær til litt kalkrik sand- og grus-rasmark Kalkinnhold d,e,f: vannrett skravur. Dominerende kornstørrelse C,D: firkant 1.0 mm	 **TD01-02** Intermediær til litt kalkrik sand- og grus-rasmark Kalkinnhold d,e,f: vannrett skravur. Dominerende kornstørrelse C,D: firkant 1.0 mm
	 **TD01-04** Kalkfattig stein til storblokket rasmark Kalkinnhold b,c: skrå skravur. Dominerende kornstørrelse E,F,G: firkant 2.2 mm	 **TD01-04** Kalkfattig stein- og blokk-rasmark Kalkinnhold b,c: skrå skravur. Dominerende kornstørrelse E,F: firkant 1.6 mm
		 **TD01-07** Kalkfattig storblokket bakli-rasmark Kalkinnhold b,c: skrå skravur. Uttørkingseksponering 0,a,b,c: grå skravur. Dominerende kornstørrelse G: firkant 1.0 mm
	 **TD01-05** Intermediær til litt kalkrik stein til storblokket rasmark Kalkinnhold d,e,f: vannrett skravur. Dominerende kornstørrelse E,F,G: firkant 2.2 mm	 **TD01-05** Intermediær til litt kalkrik stein- og blokk-rasmark Kalkinnhold d,e,f: vannrett skravur. Dominerende kornstørrelse E,F: firkant 1.6 mm
		 **TD01-08** Intermediær til litt kalkrik storblokket bakli-rasmark Kalkinnhold d,e,f: vannrett skravur. Uttørkingseksponering 0,a,b,c: grå skravur. Dominerende kornstørrelse G: firkant 1.0 mm

1:50 000 · 2 enheter	1:20 000 · 9 enheter	1:5 000 · 12 enheter
	TD01-07 Kalkfattig storblokket tørke-eksponert rasmark Kalkinnhold b,c: skrå skravur. Uttørkingseksponering d,e,f,g: mørk rød skravur. Dominerende kornstørrelse G: firkant 1.0 mm	**TD01-10** Kalkfattig storblokket tørke-eksponert rasmark Kalkinnhold b,c: skrå skravur. Uttørkingseksponering d,e,f,g: mørk rød skravur. Dominerende kornstørrelse G: firkant 1.0 mm
	TD01-08 Intermediær til litt kalkrik storblokket tørke-eksponert rasmark Kalkinnhold d,e,f: vannrett skravur. Uttørkingseksponering d,e,f,g: mørk rød skravur. Dominerende kornstørrelse G: firkant 1.0 mm	**TD01-11** Intermediær til litt kalkrik storblokket tørke-eksponert rasmark Kalkinnhold d,e,f: vannrett skravur. Uttørkingseksponering d,e,f,g: mørk rød skravur. Dominerende kornstørrelse G: firkant 1.0 mm
TD01-02 Sterkt kalkrik rasmark Kalkinnhold g,h,i: loddrett skravur	**TD01-03** Sterkt kalkrik sand- og grus-rasmark Kalkinnhold g,h,i: loddrett skravur. Dominerende kornstørrelse C,D: firkant 1.0 mm	**TD01-03** Sterkt kalkrik sand- og grus-rasmark Kalkinnhold g,h,i: loddrett skravur. Dominerende kornstørrelse C,D: firkant 1.0 mm
	TD01-06 Sterkt kalkrik stein til storblokket rasmark Kalkinnhold g,h,i: loddrett skravur. Dominerende kornstørrelse E,F,G: firkant 2.2 mm	**TD01-06** Sterkt kalkrik stein- og blokk-rasmark Kalkinnhold g,h,i: loddrett skravur. Dominerende kornstørrelse E,F: firkant 1.6 mm
		TD01-09 Sterkt kalkrik storblokket bakli-rasmark Kalkinnhold g,h,i: loddrett skravur. Uttørkingseksponering 0,a,b,c: grå skravur. Dominerende kornstørrelse G: firkant 1.0 mm
	TD01-09 Sterkt kalkrik storblokket tørke-eksponert rasmark Kalkinnhold g,h,i: loddrett skravur. Uttørkingseksponering d,e,f,g: mørk rød skravur. Dominerende kornstørrelse G: firkant 1.0 mm	**TD01-12** Sterkt kalkrik storblokket tørke-eksponert rasmark Kalkinnhold g,h,i: loddrett skravur. Uttørkingseksponering d,e,f,g: mørk rød skravur. Dominerende kornstørrelse G: firkant 1.0 mm

TD03 Rasmarkeng

1:50 000 · 2 enheter	1:20 000 · 3 enheter	1:5 000 · 6 enheter
TD03-01 Kalkfattig til litt kalkrik rasmarkeng og -hei	**TD03-01** Kalkfattig rasmarkeng og -hei Kalkinnhold b,c: skrå skravur	**TD03-01** Kalkfattig rasmarkeng og -hei Kalkinnhold b,c: skrå skravur
	TD03-02 Intermediær til litt kalkrik rasmarkeng og -hei	**TD03-02** Intermediær til litt kalkrik rasmarkeng og -hei Kalkinnhold d,e,f: vannrett skravur
		TD03-04 Intermediær til litt kalkrik kildevannspåvirket rasmarkeng og -hei Kalkinnhold d,e,f: vannrett skravur. Kildevannspåvirkning b,c: sirkel 1.0 mm
		TD03-06 Rasmarkeng og -hei med svært sterkt raspreg Rasutsatthet d: vinkel 1.0 mm
TD03-02 Klart kalkrik rasmarkeng og -hei Kalkinnhold g,h,i: loddrett skravur	**TD03-03** Klart kalkrik rasmarkeng og -hei Kalkinnhold g,h,i: loddrett skravur	**TD03-03** Klart kalkrik rasmarkeng og -hei Kalkinnhold g,h,i: loddrett skravur

1:50 000 · 2 enheter

1:20 000 · 3 enheter

1:5 000 · 6 enheter



TD03-05
Klart kalkrik kildevannspåvirket rasmarkeng og -hei
Kalkinnhold g,h,i: loddrett skravur. Kildevannspåvirkning b,c: sirkel 1.0 mm

TE02 Aktiv skredmark

1:50 000 · 3 enheter



TE02-01
Leir- og siltskred
Dominerende kornstørrelse A,B: firkant 1.0 mm



TE02-02
Sandskred
Dominerende kornstørrelse C: firkant 1.6 mm




TE02-03
Grusskred
Dominerende kornstørrelse D: firkant 2.2 mm


1:20 000 · 3 enheter



TE02-01
Leir- og siltskred
Dominerende kornstørrelse A,B: firkant 1.0 mm



TE02-02
Sandskred
Dominerende kornstørrelse C: firkant 1.6 mm



TE02-03
Grusskred
Dominerende kornstørrelse D: firkant 2.2 mm

1:5 000 · 3 enheter



TE02-01
Leir- og siltskred
Dominerende kornstørrelse A,B: firkant 1.0 mm



TE02-02
Sandskred
Dominerende kornstørrelse C: firkant 1.6 mm



TE02-03
Grusskred
Dominerende kornstørrelse D: firkant 2.2 mm

TD02 Flomskredmark

1:50 000 · 1 enheter



TD02-01
Flomskredmark

1:20 000 · 1 enheter



TD02-01
Flomskredmark

1:5 000 · 2 enheter



TD02-01
Noe utsatt flomskredmark



TD02-02
Sterkt til disruptivt utsatt flomskredmark
Flomskredutsatthet d,y: vinkel 1.0 mm

TE05 Oppfrysingsmark

1:50 000 · 2 enheter



TE05-01
Kalkfattig til litt kalkrik oppfrysingsmark



TE05-02
Sterkt kalkrik oppfrysingsmark
Kalkinnhold g,h,i: loddrett skravur

1:20 000 · 3 enheter



TE05-01
Kalkfattig oppfrysingsmark
Kalkinnhold b,c: skrå skravur. Dominerende kornstørrelse C,D,E,F,G: firkant 1.6 mm



TE05-02
Intermediær til litt kalkrik oppfrysingsmark
Kalkinnhold d,e,f,g,h,i: vannrett skravur. Dominerende kornstørrelse A,B,C,D,E,F,G: firkant 1.0 mm




TE05-03
Sterkt kalkrik oppfrysingsmark
Kalkinnhold g,h,i: loddrett skravur. Dominerende kornstørrelse A,B,C,D,E,F,G: firkant 1.0 mm


1:5 000 · 3 enheter



TE05-01
Kalkfattig oppfrysingsmark
Kalkinnhold b,c: skrå skravur. Dominerende kornstørrelse C,D,E,F,G: firkant 1.6 mm



TE05-02
Intermediær til litt kalkrik oppfrysingsmark
Kalkinnhold d,e,f,g,h,i: vannrett skravur. Dominerende kornstørrelse A,B,C,D,E,F,G: firkant 1.0 mm



TE05-03
Sterkt kalkrik oppfrysingsmark
Kalkinnhold g,h,i: loddrett skravur. Dominerende kornstørrelse A,B,C,D,E,F,G: firkant 1.0 mm

TE09 Isinnfrysingsmark

1:50 000 · 3 enheter



TE09-01
Kalkfattig isinnfrysingsmark
Kalkinnhold b,c: skrå skravur



TE09-02
Intermediær til litt kalkrik isinnfrysingsmark
Kalkinnhold d,e,f: vannrett skravur




TE09-03
Klart kalkrik isinnfrysingsmark
Kalkinnhold g,h,i: loddrett skravur

1:20 000 · 3 enheter



TE09-01
Kalkfattig isinnfrysingsmark
Kalkinnhold b,c: skrå skravur



TE09-02
Intermediær til litt kalkrik isinnfrysingsmark
Kalkinnhold d,e,f: vannrett skravur



TE09-03
Klart kalkrik isinnfrysingsmark
Kalkinnhold g,h,i: loddrett skravur

1:5 000 · 3 enheter



TE09-01
Kalkfattig isinnfrysingsmark
Kalkinnhold b,c: skrå skravur



TE09-02
Intermediær til litt kalkrik isinnfrysingsmark
Kalkinnhold d,e,f: vannrett skravur



TE09-03
Klart kalkrik isinnfrysingsmark
Kalkinnhold g,h,i: loddrett skravur

TM01 Hard sterkt endret fastmark

1:50 000 · 1 enheter



TM01-01
Hard sterkt endret fastmark

1:20 000 · 3 enheter



TM01-01
Hard sterkt endret fastmark av lite modifisert substrat



TM01-02
Hulrom i hard sterkt endret fastmark
Grottebetinget skjerming b,c,d,y: vinkel 1.0 mm



TM01-03
Hard sterkt endret fastmark av sterkt modifisert eller endret substrat
Fysisk menneskepåvirket fastmark B: ring 1.0 mm

1:5 000 · 3 enheter



TM01-01
Hard sterkt endret fastmark av lite modifisert substrat



TM01-02
Hulrom i hard sterkt endret fastmark
Grottebetinget skjerming b,c,d,y: vinkel 1.0 mm



TM01-03
Hard sterkt endret fastmark av sterkt modifisert eller endret substrat
Fysisk menneskepåvirket fastmark B: ring 1.0 mm

TM02 Ny hard fastmark på tørrlagt ferskvannsbunn

Gjelder alle enheter: Blå sirkel: tidligere ferskvannsbunn.

1:50 000 · 2 enheter




TM02-01
Ny hard fastmark på tørrlagt innsjøbunn
Blå sirkel: tidligere ferskvannsbunn. Fysisk menneskepåvirket fastmark C: ring 1.0 mm




TM02-02
Ny hard fastmark på tørrlagt elvebunn
Blå sirkel: tidligere ferskvannsbunn. Fysisk menneskepåvirket fastmark D: ring 1.6 mm

1:20 000 · 2 enheter



TM02-01
Ny hard fastmark på tørrlagt innsjøbunn
Blå sirkel: tidligere ferskvannsbunn. Fysisk menneskepåvirket fastmark C: ring 1.0 mm



TM02-02
Ny hard fastmark på tørrlagt elvebunn
Blå sirkel: tidligere ferskvannsbunn. Fysisk menneskepåvirket fastmark D: ring 1.6 mm

1:5 000 · 2 enheter



TM02-01
Ny hard fastmark på tørrlagt innsjøbunn
Blå sirkel: tidligere ferskvannsbunn. Fysisk menneskepåvirket fastmark C: ring 1.0 mm



TM02-02
Ny hard fastmark på tørrlagt elvebunn
Blå sirkel: tidligere ferskvannsbunn. Fysisk menneskepåvirket fastmark D: ring 1.6 mm

TM03 Løs sterkt endret fastmark


1:50 000 · 5 enheter



TM03-01
Sterkt endret fastmark med dekke av jord eller blandet sediment
Fysisk menneskepåvirket fastmark E: ring 1.0 mm



TM03-02
Sterkt endret fastmark med dekke av leire til grus
Dominerende kornstørrelse A,B,C,D: firkant 1.6 mm. Fysisk menneskepåvirket fastmark E: ring 1.0 mm



TM03-03
Sterkt endret fastmark av substrat preget av kjemisk påvirkning
Fysisk menneskepåvirket fastmark F: ring 1.6 mm



TM03-04
Sterkt endret fastmark av organisk avfall




TM03-05
Sterkt endret fastmark av løst, sterkt modifisert eller syntetisk substrat
Skilles fra naboenhet med symbol: vinkel 1.0 mm


1:20 000 · 7 enheter



TM03-01
Sterkt endret fastmark med dekke av jord eller blandet sediment
Fysisk menneskepåvirket fastmark E: ring 1.0 mm



TM03-02
Sterkt endret fastmark med dekke av leire til grus
Dominerende kornstørrelse A,B,C,D: firkant 1.6 mm. Fysisk menneskepåvirket fastmark E: ring 1.0 mm



TM03-03
Sterkt endret fastmark av substrat preget av kjemisk påvirkning
Fysisk menneskepåvirket fastmark F: ring 1.6 mm



TM03-04
Sterkt endret fastmark av grovt organisk avfall
Fysisk menneskepåvirket fastmark G: ring 2.2 mm



TM03-05
Sterkt endret fastmark av fint organisk avfall



TM03-06
Sterkt endret fastmark av løst, sterkt modifisert eller syntetisk substrat
Skilles fra naboenhet med symbol: vinkel 1.0 mm



TM03-07
Sterkt endret fastmark av ikke-konsolidert løst, sterkt modifisert eller syntetisk substrat
Skilles fra naboenhet med symbol: stjerne 1.0 mm

1:5 000 · 8 enheter




TM03-01
Sterkt endret fastmark med dekke av jord eller blandet sediment
Fysisk menneskepåvirket fastmark E: ring 1.0 mm



TM03-02
Sterkt endret fastmark med dekke av leire og silt
Dominerende kornstørrelse A,B: firkant 1.0 mm. Fysisk menneskepåvirket fastmark E: ring 1.0 mm



TM03-03
Sterkt endret fastmark med dekke av sand og grus
Dominerende kornstørrelse C,D: firkant 2.2 mm. Fysisk menneskepåvirket fastmark E: ring 1.0 mm



TM03-04
Sterkt endret fastmark av substrat preget av kjemisk påvirkning
Fysisk menneskepåvirket fastmark F: ring 1.6 mm



TM03-05
Sterkt endret fastmark av grovt organisk avfall
Fysisk menneskepåvirket fastmark G: ring 2.2 mm



TM03-06
Sterkt endret fastmark av fint organisk avfall



TM03-07
Sterkt endret fastmark av konsolidert løst, sterkt modifisert eller syntetisk substrat
Skilles fra naboenhet med symbol: vinkel 1.0 mm



TM03-08
Sterkt endret fastmark av ikke-konsolidert løst, sterkt modifisert eller syntetisk substrat
Skilles fra naboenhet med symbol: stjerne 1.0 mm

TM04 Ny løs fastmark på tørrlagt ferskvannsbunn

Gjelder alle enheter: Blå sirkel: tidligere ferskvannsbunn.

1:50 000 · 2 enheter



TM04-01
Ny løs fastmark på tørrlagt innsjøbunn
Blå sirkel: tidligere ferskvannsbunn. Fysisk menneskepåvirket fastmark K: ring 1.0 mm



TM04-02
Ny løs fastmark på tørrlagt elvebunn
Blå sirkel: tidligere ferskvannsbunn. Fysisk menneskepåvirket fastmark L: ring 1.6 mm

1:20 000 · 2 enheter



TM04-01
Ny løs fastmark på tørrlagt innsjøbunn
Blå sirkel: tidligere ferskvannsbunn. Fysisk menneskepåvirket fastmark K: ring 1.0 mm



TM04-02
Ny løs fastmark på tørrlagt elvebunn
Blå sirkel: tidligere ferskvannsbunn. Fysisk menneskepåvirket fastmark L: ring 1.6 mm

1:5 000 · 2 enheter



TM04-01
Ny løs fastmark på tørrlagt innsjøbunn
Blå sirkel: tidligere ferskvannsbunn. Fysisk menneskepåvirket fastmark K: ring 1.0 mm



TM04-02
Ny løs fastmark på tørrlagt elvebunn
Blå sirkel: tidligere ferskvannsbunn. Fysisk menneskepåvirket fastmark L: ring 1.6 mm

TM05 Ny løs fastmark på drenert våtmark

Gjelder alle enheter: Blå sirkel: tidligere våtmark.

1:50 000 · 1 enheter




TM05-01
Ny løs fastmark på drenert våtmark
Blå sirkel: tidligere våtmark

1:20 000 · 1 enheter




TM05-01
Ny løs fastmark på drenert våtmark
Blå sirkel: tidligere våtmark

1:5 000 · 2 enheter



TM05-01
Ny løs fastmark på drenert jordvannsmyr
Blå sirkel: tidligere våtmark. Fysisk menneskepåvirket fastmark M: ring 1.0 mm



TM05-02
Ny løs fastmark på drenert nedbørsmyr
Blå sirkel: tidligere våtmark. Fysisk menneskepåvirket fastmark N: ring 2.2 mm

V Våtmarkssystemer

VA01 Åpen jordvannsmyr

1:50 000 · 2 enheter



VA01-01
Svært kalkfattig til litt kalkrik mykmatte til øvre tuenivå

1:20 000 · 4 enheter



VA01-01
Svært kalkfattig til svakt intermediær mykmatte til øvre tuenivå
Kalkinnhold a,b,c,d: skrå skravur. Myrflatepreg a,b,c,d: heltrukken skravur

1:5 000 · 19 enheter



VA01-01
Temmelig til svært kalkfattig mykmatte til øvre fastmatte
Kalkinnhold a,b: skrå skravur. Tørrleggingsvarighet c,d,e,f,g,h: oransje skravur. Myrflatepreg c,d: heltrukken skravur



VA01-02
Temmelig til svært kalkfattig tuenivå
Kalkinnhold a,b: skrå skravur. Tørrleggingsvarighet i,j,k: mørk rød skravur. Myrflatepreg c,d: heltrukken skravur



VA01-03
Litt kalkfattig til svakt intermediær mykmatte til øvre fastmatte
Kalkinnhold c,d: skrå skravur. Tørrleggingsvarighet c,d,e,f,g,h: oransje skravur. Myrflatepreg c,d: heltrukken skravur. Skilles fra naboenhet med symbol: vinkel 1.0 mm



VA01-04
Litt kalkfattig til svakt intermediært nedre tuenivå
Kalkinnhold c,d: skrå skravur. Tørrleggingsvarighet i,j: mørk rød skravur. Myrflatepreg c,d: heltrukken skravur. Skilles fra naboenhet med symbol: vinkel 1.0 mm



VA01-10
Temmelig til svært kalkfattig mattenivå i myrkant
Kalkinnhold a,b: skrå skravur. Tørrleggingsvarighet c,d,e,f,g,h: oransje skravur. Myrflatepreg a,b: stiplet skravur



VA01-11
Temmelig til svært kalkfattig tuenivå i myrkant
Kalkinnhold a,b: skrå skravur. Tørrleggingsvarighet i,j,k: mørk rød skravur. Myrflatepreg a,b: stiplet skravur

1:50 000 · 2 enheter	1:20 000 · 4 enheter	1:5 000 · 19 enheter
		VA01-12 Litt kalkfattig til svakt intermediært mattenivå i myrkant Kalkinnhold c,d: skrå skravur. Tørrleggingsvarighet c,d,e,f,g,h: oransje skravur. Myrflatepreg a,b: stiplet skravur. Skilles fra naboenhet med symbol: vinkel 1.0 mm
		VA01-13 Litt kalkfattig til svakt intermediært tuenivå i myrkant Kalkinnhold c,d: skrå skravur. Tørrleggingsvarighet i,j,k: mørk rød skravur. Myrflatepreg a,b: stiplet skravur. Skilles fra naboenhet med symbol: vinkel 1.0 mm
	VA01-02 Sterkt intermediær til litt kalkrikt mattenivå i myrkant til tuenivå Kalkinnhold d,e,f: vannrett skravur. Myrflatepreg a,b,c,d: heltrukken skravur	**VA01-05** Sterkt intermediær til litt kalkrik mykmatte til øvre fastmatte Kalkinnhold e,f: vannrett skravur. Tørrleggingsvarighet c,d,e,f,g,h: oransje skravur. Myrflatepreg c,d: heltrukken skravur
		VA01-06 Sterkt intermediær til litt kalkrikt nedre tuenivå Kalkinnhold e,f: vannrett skravur. Tørrleggingsvarighet i,j: mørk rød skravur. Myrflatepreg c,d: heltrukken skravur
		VA01-14 Sterkt intermediær til litt kalkrikt mattenivå i myrkant Kalkinnhold d,e,f: vannrett skravur. Tørrleggingsvarighet c,d,e,f,g,h: oransje skravur. Myrflatepreg a,b: stiplet skravur
		VA01-15 Sterkt intermediær til litt kalkrikt tuenivå i myrkant Kalkinnhold e,f: vannrett skravur. Tørrleggingsvarighet i,j,k: mørk rød skravur. Myrflatepreg a,b: stiplet skravur
	VA01-04 Kalkrikt mattenivå i myrkant med saltpåvirkning Kalkinnhold e,f,g,h: vannrett skravur. Tørrleggingsvarighet c,d,e,f,g,h: oransje skravur. Myrflatepreg a,b: stiplet skravur. Marin salinitet b,c,d: plusstegn 1.0 mm	**VA01-19** Kalkrikt mattenivå i myrkant med saltpåvirkning Kalkinnhold e,f,g,h: vannrett skravur. Tørrleggingsvarighet c,d,e,f,g,h: oransje skravur. Myrflatepreg a,b: stiplet skravur. Marin salinitet b,c,d: plusstegn 1.0 mm
VA01-02 Temmelig til ekstremt kalkrikt mattenivå i myrkant til nedre tuenivå Kalkinnhold g,h,i: loddrett skravur	**VA01-03** Temmelig til ekstremt kalkrikt mattenivå i myrkant til nedre tuenivå Kalkinnhold g,h,i: loddrett skravur. Myrflatepreg a,b,c,d: heltrukken skravur	**VA01-07** Temmelig kalkrik mykmatte til øvre fastmatte Kalkinnhold g,h: loddrett skravur. Tørrleggingsvarighet c,d,e,f,g,h: oransje skravur. Myrflatepreg c,d: heltrukken skravur
		VA01-08 Temmelig til ekstremt kalkrikt nedre tuenivå Kalkinnhold g,h,i: loddrett skravur. Tørrleggingsvarighet i,j: mørk rød skravur. Myrflatepreg c,d: heltrukken skravur
		VA01-09 Ekstremt kalkrik mykmatte til øvre fastmatte Kalkinnhold i: loddrett skravur. Tørrleggingsvarighet c,d,e,f,g,h: oransje skravur. Myrflatepreg c,d: heltrukken skravur. Skilles fra naboenhet med symbol: vinkel 1.0 mm
		VA01-16 Temmelig kalkrikt mattenivå i myrkant Kalkinnhold g,h: loddrett skravur. Tørrleggingsvarighet c,d,e,f,g,h: oransje skravur. Myrflatepreg a,b: stiplet skravur

1:50 000 · 2 enheter

1:20 000 · 4 enheter

1:5 000 · 19 enheter



VA01-17
Ekstremt kalkrikt mattenivå i myrkant
Kalkinnhold i: loddrett skravur. Tørrleggingsvarighet c,d,e,f,g,h: oransje skravur. Myrflatepreg a,b: stiplet skravur. Skilles fra naboenhet med symbol: vinkel 1.0 mm



VA01-18
Temmelig til ekstremt kalkrikt nedre tuenivå i myrkant
Kalkinnhold g,h,i: loddrett skravur. Tørrleggingsvarighet i,j: mørk rød skravur. Myrflatepreg a,b: stiplet skravur

VC01 Åpen nedbørsmyr

1:50 000 · 1 enheter




VC01-01
Åpen nedbørsmyr

1:20 000 · 2 enheter



VC01-01
Åpen nedbørsmyr uten permafrost



VC01-02
Rabbepreget nedbørsmyr-myrtue på permafrost
Tørrleggingsvarighet i,j,k: mørk rød skravur. Vindutsatthet b: strek 1.0 mm. Permafrost A: vinkel 1.0 mm

1:5 000 · 3 enheter



VC01-01
Nedbørsmyr-mykmatte og fastmatte
Tørrleggingsvarighet c,d,e,f,g,h: oransje skravur. Myrflatepreg c,d: heltrukken skravur



VC01-02
Nedbørsmyr-tuenivå
Tørrleggingsvarighet i,j,k: mørk rød skravur. Myrflatepreg a,b,c,d: heltrukken skravur



VC01-03
Rabbepreget nedbørsmyr-myrtue på permafrost
Tørrleggingsvarighet i,j,k: mørk rød skravur. Myrflatepreg a,b,c,d: heltrukken skravur. Vindutsatthet b: strek 1.0 mm. Permafrost A: vinkel 1.0 mm

VG01 Ny naturgitt torvmark

1:50 000 · 1 enheter



VG01-01
Ny naturgitt torvmark

1:20 000 · 2 enheter



VG01-01
Ny naturgitt torvmark med jordvannstilførsel eller kildepreg




VG01-02
Ny naturgitt torvmark med innsjø- eller elvevannstilførsel
Vanntilførsel A,B: rute 1.0 mm

1:5 000 · 2 enheter



VG01-01
Ny naturgitt torvmark med jordvannstilførsel eller kildepreg




VG01-02
Ny naturgitt torvmark med innsjø- eller elvevannstilførsel
Vanntilførsel A,B: rute 1.0 mm

VC05 Permafrost-våtmark

Gjelder alle enheter: Skravur i fargen til oppfrysingsmark: kobler frostpreget våtmark til oppfrysingsmark.

1:50 000 · 1 enheter



VC05-01
Permafrost-våtmark
Skravur i fargen til oppfrysingsmark: kobler frostpreget våtmark til oppfrysingsmark

1:20 000 · 1 enheter



VC05-01
Permafrost-våtmark
Skravur i fargen til oppfrysingsmark: kobler frostpreget våtmark til oppfrysingsmark

1:5 000 · 2 enheter



VC05-01
Permafrost-våtmark i nedre mykmatte-nedre fastmattenivå
Skravur i fargen til oppfrysingsmark: kobler frostpreget våtmark til oppfrysingsmark. Skilles fra naboenhet med prikket skravur



VC05-02
Fast og tuet, knapt kildepåvirket permafrost-våtmark
Skravur i fargen til oppfrysingsmark: kobler frostpreget våtmark til oppfrysingsmark

VE01 Oppfrysingsvåtmark

Gjelder alle enheter: Skravur i fargen til oppfrysingsmark: kobler frostpreget våtmark til oppfrysingsmark.

1:50 000 · 1 enheter



VE01-01
Oppfrysingsvåtmark
Skravur i fargen til oppfrysingsmark: kobler frostpreget våtmark til oppfrysingsmark

1:20 000 · 2 enheter



VE01-01
Kalkfattig til litt kalkrik oppfrysingsvåtmark
Kalkinnhold c,d,e,f: vannrett skravur. Skravur i fargen til oppfrysingsmark: kobler frostpreget våtmark til oppfrysingsmark



VE01-02
Temmelig til ekstremt kalkrik oppfrysingsvåtmark
Kalkinnhold g,h,i: loddrett skravur. Skravur i fargen til oppfrysingsmark: kobler frostpreget våtmark til oppfrysingsmark

1:5 000 · 2 enheter



VE01-01
Kalkfattig til litt kalkrik oppfrysingsvåtmark
Kalkinnhold c,d,e,f: vannrett skravur. Skravur i fargen til oppfrysingsmark: kobler frostpreget våtmark til oppfrysingsmark



VE01-02
Temmelig til ekstremt kalkrik oppfrysingsvåtmark
Kalkinnhold g,h,i: loddrett skravur. Skravur i fargen til oppfrysingsmark: kobler frostpreget våtmark til oppfrysingsmark

VG02 Ny naturgitt grunn våtmark

1:50 000 · 1 enheter




VG02-01
Ny naturgitt grunn våtmark

1:20 000 · 2 enheter



VG02-01
Ny naturgitt grunn våtmark med jordvannstilførsel eller kildepreg



VG02-02
Ny naturgitt grunn våtmark med innsjø- eller elvevannstilførsel
Vanntilførsel A,B: rute 1.0 mm

1:5 000 · 2 enheter



VG02-01
Ny naturgitt grunn våtmark med jordvannstilførsel eller kildepreg



VG02-02
Ny naturgitt grunn våtmark med innsjø- eller elvevannstilførsel
Vanntilførsel A,B: rute 1.0 mm

VC02 Torvmarkskilde

1:50 000 · 1 enheter



VC02-01
Torvmarkskilde

1:20 000 · 2 enheter



VC02-01
Litt kalkfattig til litt kalkrik torvmarkskilde
Kalkinnhold c,d,e,f: vannrett skravur

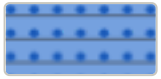


VC02-02
Klart kalkrik torvmarkskilde
Kalkinnhold g,h,i: loddrett skravur

1:5 000 · 3 enheter



VC02-01
Litt kalkfattig til svakt intermediær svak eller ustabil torvmarkskilde
Kalkinnhold c,d: skrå skravur. Kildevannspåvirkning d,e: sirkel 1.0 mm



VC02-02
Sterkt intermediær til litt kalkrik torvmarkskilde
Kalkinnhold e,f: vannrett skravur. Kildevannspåvirkning d,e,y: sirkel 1.6 mm



VC02-03
Temmelig til ekstremt kalkrik torvmarkskilde
Kalkinnhold g,h,i: loddrett skravur. Kildevannspåvirkning d,e,y: sirkel 1.6 mm

VC03 Grunnkilde

1:50 000 · 1 enheter



VC03-01
Grunnkilde

1:20 000 · 2 enheter



VC03-01
Litt kalkfattig til litt kalkrik grunnkilde
Kalkinnhold c,d,e,f: vannrett skravur




VC03-02
Klart kalkrik grunnkilde
Kalkinnhold g,h,i: loddrett skravur

1:5 000 · 3 enheter



VC03-01
Litt kalkfattig til svakt intermediær svak eller ustabil grunnkilde
Kalkinnhold c,d: skrå skravur. Kildevannspåvirkning d,e: sirkel 1.0 mm



VC03-02
Sterkt intermediær til litt kalkrik grunnkilde
Kalkinnhold e,f: vannrett skravur. Kildevannspåvirkning d,e,y: sirkel 1.6 mm



VC03-03
Klart kalkrik grunnkilde
Kalkinnhold g,h,i: loddrett skravur. Kildevannspåvirkning d,e,y: sirkel 1.6 mm

VC04 Våt- og kildesnøleie

Gjelder alle enheter: Skravur i fargen til snøleie: kobler våtsnøleie til snøleie.

1:50 000 · 1 enheter



VC04-01
Våt- og kildesnøleie
Skravur i fargen til snøleie: kobler våtsnøleie til snøleie

1:20 000 · 4 enheter


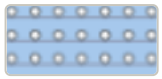

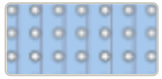



VC04-01
Kalkfattig til litt rikt moderat våtsnøleie og kildepåvirket snøleie
Kalkinnhold c,d,e,f: vannrett skravur. Skravur i fargen til snøleie: kobler våtsnøleie til snøleie. Snødekkebetinget vekstsesongreduksjon a,b: sirkel 1.0 mm

1:5 000 · 10 enheter



VC04-01
Kalkfattig til litt rikt moderat våtsnøleie og kildepåvirket snøleie
Kalkinnhold c,d,e,f: vannrett skravur. Skravur i fargen til snøleie: kobler våtsnøleie til snøleie. Snødekkebetinget vekstsesongreduksjon a,b: sirkel 1.0 mm

1:50 000 · 1 enheter	1:20 000 · 4 enheter	1:5 000 · 10 enheter
	 **VC04-02** Sterkt kalkrikt våtsnøleie og kildepåvirket snøleie Kalkinnhold g,h,i: loddrett skravur. Skravur i fargen til snøleie: kobler våtsnøleie til snøleie. Snødekkebetinget vekstsesongreduksjon a,b: sirkel 1.0 mm	 **VC04-02** Sterkt kalkrikt våtsnøleie og kildepåvirket snøleie Kalkinnhold g,h,i: loddrett skravur. Skravur i fargen til snøleie: kobler våtsnøleie til snøleie. Snødekkebetinget vekstsesongreduksjon a,b: sirkel 1.0 mm
	 **VC04-03** Kalkfattig til litt rikt sent våtsnøleie og kilde-utgaver av snøleie Kalkinnhold c,d,e,f: vannrett skravur. Skravur i fargen til snøleie: kobler våtsnøleie til snøleie. Snødekkebetinget vekstsesongreduksjon c,d,e,f: sirkel 1.0 mm	 **VC04-03** Kalkfattig til litt rikt seint våtsnøleie eller kildepåvirket snøleie Kalkinnhold c,d,e,f: vannrett skravur. Skravur i fargen til snøleie: kobler våtsnøleie til snøleie. Snødekkebetinget vekstsesongreduksjon c,d: sirkel 1.6 mm
		 **VC04-05** Kalkfattig til litt rikt seint kildesnøleie Kalkinnhold c,d,e,f: vannrett skravur. Skravur i fargen til snøleie: kobler våtsnøleie til snøleie. Kildevannspåvirkning d,e: sirkel 1.6 mm. Snødekkebetinget vekstsesongreduksjon c,d: sirkel 1.6 mm
		 **VC04-07** Kalkfattig til litt rikt ekstremt, kildepåvirket snøleie Kalkinnhold c,d,e,f: vannrett skravur. Skravur i fargen til snøleie: kobler våtsnøleie til snøleie. Kildevannspåvirkning b,c: sirkel 1.0 mm. Snødekkebetinget vekstsesongreduksjon e,f: sirkel 1.6 mm
		 **VC04-09** Kalkfattig til litt rikt ekstrem-kildesnøleie Kalkinnhold c,d,e,f: vannrett skravur. Skravur i fargen til snøleie: kobler våtsnøleie til snøleie. Kildevannspåvirkning d,e: sirkel 1.6 mm. Snødekkebetinget vekstsesongreduksjon e,f: sirkel 1.6 mm
	 **VC04-04** Sterkt kalkrikt sent våtsnøleie og kilde-utgaver av snøleie Kalkinnhold g,h,i: loddrett skravur. Skravur i fargen til snøleie: kobler våtsnøleie til snøleie. Snødekkebetinget vekstsesongreduksjon c,d,e,f: sirkel 1.0 mm	 **VC04-04** Sterkt kalkrikt seint våtsnøleie eller kildepåvirket snøleie Kalkinnhold g,h,i: loddrett skravur. Skravur i fargen til snøleie: kobler våtsnøleie til snøleie. Snødekkebetinget vekstsesongreduksjon c,d: sirkel 1.6 mm
		 **VC04-06** Temmelig til ekstremt kalkrikt seint kildesnøleie Kalkinnhold g,h,i: loddrett skravur. Skravur i fargen til snøleie: kobler våtsnøleie til snøleie. Kildevannspåvirkning d,e: sirkel 1.6 mm. Snødekkebetinget vekstsesongreduksjon c,d: sirkel 1.6 mm
		 **VC04-08** Sterkt kalkrikt ekstremt, kildepåvirket snøleie Kalkinnhold g,h,i: loddrett skravur. Skravur i fargen til snøleie: kobler våtsnøleie til snøleie. Kildevannspåvirkning b,c: sirkel 1.0 mm. Snødekkebetinget vekstsesongreduksjon e,f: sirkel 1.6 mm
		 **VC04-10** Sterkt kalkrikt ekstrem-kildesnøleie Kalkinnhold g,h,i: loddrett skravur. Skravur i fargen til snøleie: kobler våtsnøleie til snøleie. Kildevannspåvirkning d,e: sirkel 1.6 mm. Snødekkebetinget vekstsesongreduksjon e,f: sirkel 1.6 mm

VB01 Myr- og sumpskogsmark

Gjelder alle enheter: Grønn sirkel: skog i våtmark.

1:50 000 · 2 enheter



VB01-01
Svært kalkfattig til litt kalkrik myr- og sumpskogsmark
Grønn sirkel: skog i våtmark




VB01-02
Klart kalkrik myr- og sumpskogsmark
Grønn sirkel: skog i våtmark. Kalkinnhold g,h,i: loddrett skravur

1:20 000 · 3 enheter



VB01-01
Svært kalkfattig til svakt intermediær myr- og sumpskogsmark
Grønn sirkel: skog i våtmark. Kalkinnhold a,b,c,d,e,f: skrå skravur



VB01-02
Sterkt intermediær til litt kalkrik myr- og sumpskogsmark
Grønn sirkel: skog i våtmark. Kalkinnhold e,f,g,h: vannrett skravur




VB01-03
Klart kalkrik myr- og sumpskogsmark
Grønn sirkel: skog i våtmark. Kalkinnhold g,h,i: loddrett skravur


1:5 000 · 4 enheter



VB01-01
Svært til temmelig kalkfattig myr- og sumpskogsmark
Grønn sirkel: skog i våtmark. Kalkinnhold a,b: skrå skravur



VB01-02
Litt kalkfattig til svakt intermediær kildesumpskogsmark, myr- og sumpskogsmark
Grønn sirkel: skog i våtmark. Kalkinnhold c,d,e,f: vannrett skravur



VB01-03
Sterkt intermediær til litt kalkrik kildesumpskogsmark, myr- og sumpskogsmark
Grønn sirkel: skog i våtmark. Kalkinnhold e,f: vannrett skravur. Skilles fra naboenhet med prikket skravur



VB01-04
Klart kalkrik kildesumpskogsmark, myr- og sumpskogsmark
Grønn sirkel: skog i våtmark. Kalkinnhold g,h,i: loddrett skravur

VF01 Nedbørsmyr-skogsmark

Gjelder alle enheter: Grønn sirkel: skog i våtmark.

1:50 000 · 1 enheter



VF01-01
Nedbørsmyr-skogsmark
Grønn sirkel: skog i våtmark

1:20 000 · 1 enheter



VF01-01
Nedbørsmyr-skogsmark
Grønn sirkel: skog i våtmark

1:5 000 · 1 enheter

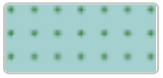


VF01-01
Nedbørsmyr-skogsmark
Grønn sirkel: skog i våtmark

VF02 Strandsumpskogsmark

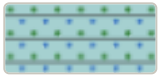
Gjelder alle enheter: Grønn sirkel: skog i våtmark.

1:50 000 · 1 enheter



VF02-01
Strandsumpskogsmark
Grønn sirkel: skog i våtmark

1:20 000 · 3 enheter

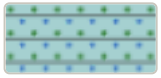


VF02-01
Intermediær til litt kalkrik innsjø-strandsumpskogsmark
Grønn sirkel: skog i våtmark. Kalkinnhold d,e,f: vannrett skravur. Vanntilførsel A: rute 1.0 mm



VF02-02
Kalkrik innsjø-strandsumpskogsmark
Grønn sirkel: skog i våtmark. Kalkinnhold g,h: loddrett skravur. Vanntilførsel A: rute 1.0 mm



1:5 000 · 3 enheter



VF02-01
Intermediær til litt kalkrik innsjø-strandsumpskogsmark
Grønn sirkel: skog i våtmark. Kalkinnhold d,e,f: vannrett skravur. Vanntilførsel A: rute 1.0 mm










VF02-02
Kalkrik innsjø-strandsumpskogsmark
Grønn sirkel: skog i våtmark. Kalkinnhold g,h: loddrett skravur. Vanntilførsel A: rute 1.0 mm

1:50 000 · 1 enheter	1:20 000 · 3 enheter	1:5 000 · 3 enheter
	 **VF02-03** Kalkrik saltpåvirket hav-strandsumpskogsmark Grønn sirkel: skog i våtmark. Kalkinnhold g,h: loddrett skravur. Vanntilførsel D: rute 2.2 mm	 **VF02-03** Kalkrik saltpåvirket hav-strandsumpskogsmark Grønn sirkel: skog i våtmark. Kalkinnhold g,h: loddrett skravur. Vanntilførsel D: rute 2.2 mm



VI01 Klart endret våtmarksskogsmark

Gjelder alle enheter: Grønn sirkel: skog i våtmark.

1:50 000 · 1 enheter	1:20 000 · 4 enheter	1:5 000 · 4 enheter
 **VI01-01** Klart endret våtmarksskogsmark Grønn sirkel: skog i våtmark	 **VI01-01** Ikke-kalkrik grøftet våtmarksskogsmark Grønn sirkel: skog i våtmark. Kalkinnhold b,c,d,e,f: vannrett skravur	 **VI01-01** Ikke-kalkrik grøftet våtmarksskogsmark Grønn sirkel: skog i våtmark. Kalkinnhold b,c,d,e,f: vannrett skravur
	 **VI01-02** Ikke-kalkrik våtmarksskogsmark med treslagsskifte eller tilplanting Grønn sirkel: skog i våtmark. Kalkinnhold b,c,d,e,f: vannrett skravur. Fysisk menneskepåvirket våtmark G: ring 1.0 mm	 **VI01-02** Ikke-kalkrik våtmarksskogsmark med treslagsskifte eller tilplanting Grønn sirkel: skog i våtmark. Kalkinnhold b,c,d,e,f: vannrett skravur. Fysisk menneskepåvirket våtmark G: ring 1.0 mm
	 **VI01-03** Grøftet våtmarks-kalkskogsmark Grønn sirkel: skog i våtmark. Kalkinnhold g,h,i: loddrett skravur	 **VI01-03** Grøftet våtmarks-kalkskogsmark Grønn sirkel: skog i våtmark. Kalkinnhold g,h,i: loddrett skravur
	 **VI01-04** Våtmarks-kalkskogsmark med treslagsskifte eller tilplanting Grønn sirkel: skog i våtmark. Kalkinnhold g,h,i: loddrett skravur. Fysisk menneskepåvirket våtmark G: ring 1.0 mm	 **VI01-04** Våtmarks-kalkskogsmark med treslagsskifte eller tilplanting Grønn sirkel: skog i våtmark. Kalkinnhold g,h,i: loddrett skravur. Fysisk menneskepåvirket våtmark G: ring 1.0 mm

VK01 Slåttemyr

Gjelder alle enheter: Gul skravur: semi-naturlig.

1:50 000 · 1 enheter	1:20 000 · 2 enheter	1:5 000 · 3 enheter
 **VK01-01** Slåttemyr Gul skravur: semi-naturlig	 **VK01-01** Kalkfattig til litt rik slåttemyr Kalkinnhold b,c,d,e,f: vannrett skravur. Gul skravur: semi-naturlig	 **VK01-01** Kalkfattig til svakt intermediær slåttemyr Kalkinnhold b,c,d: skrå skravur. Gul skravur: semi-naturlig
		 **VK01-02** Sterkt intermediær til litt kalkrik slåttemyr Kalkinnhold e,f: vannrett skravur. Gul skravur: semi-naturlig
	 **VK01-02** Kalkrik slåttemyr Kalkinnhold g,h,i: loddrett skravur. Gul skravur: semi-naturlig	 **VK01-03** Kalkrik slåttemyr Kalkinnhold g,h,i: loddrett skravur. Gul skravur: semi-naturlig

VK02 Semi-naturlig våteng


Gjelder alle enheter: Gul skravur: semi-naturlig.

1:50 000 · 1 enheter



VK02-01
Semi-naturlig våteng
Gul skravur: semi-naturlig

1:20 000 · 2 enheter



VK02-01
Kalkfattig til litt kalkrik semi-naturlig våteng
Kalkinnhold b,c,d,e,f: vannrett skravur. Gul skravur: semi-naturlig




VK02-02
Klart kalkrik semi-naturlig våteng
Kalkinnhold d,e,f,g,h,i: vannrett skravur. Gul skravur: semi-naturlig. Skilles fra naboenhet med prikket skravur

1:5 000 · 3 enheter



VK02-01
Kalkfattig til svakt intermediær semi-naturlig våteng
Gul skravur: semi-naturlig



VK02-02
Sterkt intermediær til litt kalkrik semi-naturlig våteng
Kalkinnhold e,f: vannrett skravur. Gul skravur: semi-naturlig



VK02-03
Klart kalkrik semi-naturlig våteng
Kalkinnhold g,h,i: loddrett skravur. Gul skravur: semi-naturlig

VM01 Sterkt endret torvmark

Gjelder alle enheter: Blå skravur: opphav i myr.

1:50 000 · 1 enheter



VM01-01
Sterkt endret torvmark
Blå skravur: opphav i myr


1:20 000 · 5 enheter



VM01-01
Kalkfattig til litt kalkrik grøftet jordvannsmyr
Kalkinnhold a,b,c,d,e,f: skrå skravur. Blå skravur: opphav i myr



VM01-02
Klart kalkrik grøftet jordvannsmyr
Kalkinnhold g,h,i: loddrett skravur. Blå skravur: opphav i myr



VM01-03
Grøftet nedbørsmyr
Blå skravur: opphav i myr. Vanntilførsel E: rute 1.0 mm



VM01-04
Jordvannsmyr-torvtak
Blå skravur: opphav i myr. Fysisk menneskepåvirket våtmark B: ring 1.0 mm




VM01-05
Nedbørsmyr-torvtak
Blå skravur: opphav i myr. Vanntilførsel E: rute 1.0 mm. Fysisk menneskepåvirket våtmark B: ring 1.0 mm

1:5 000 · 6 enheter



VM01-01
Kalkfattig til svakt intermediær grøftet jordvannsmyr
Kalkinnhold a,b,c,d: skrå skravur. Blå skravur: opphav i myr



VM01-02
Sterkt intermediær til litt kalkrik grøftet jordvannsmyr
Kalkinnhold e,f: vannrett skravur. Blå skravur: opphav i myr



VM01-03
Klart kalkrik grøftet jordvannsmyr
Kalkinnhold g,h,i: loddrett skravur. Blå skravur: opphav i myr



VM01-04
Grøftet nedbørsmyr
Blå skravur: opphav i myr. Vanntilførsel E: rute 1.0 mm



VM01-05
Jordvannsmyr-torvtak
Blå skravur: opphav i myr. Fysisk menneskepåvirket våtmark B: ring 1.0 mm



VM01-06
Nedbørsmyr-torvtak
Blå skravur: opphav i myr. Vanntilførsel E: rute 1.0 mm. Fysisk menneskepåvirket våtmark B: ring 1.0 mm

VM02 Ny torvmark på tidligere ferskvannsbunn

Gjelder alle enheter: Blå skravur: opphav i myr.

1:50 000 · 1 enheter	1:20 000 · 1 enheter	1:5 000 · 1 enheter
 VM02-01 Ny torvmark på tidligere ferskvannsbunn Blå skravur: opphav i myr	 VM02-01 Ny torvmark på tidligere ferskvannsbunn Blå skravur: opphav i myr	 VM02-01 Ny torvmark på tidligere ferskvannsbunn Blå skravur: opphav i myr

VM03 Ny torvmark på menneskebetinget forsumpet fastmark

Gjelder alle enheter: Blå skravur: opphav i myr.

1:50 000 · 1 enheter	1:20 000 · 1 enheter	1:5 000 · 1 enheter
 VM03-01 Ny torvmark på menneskebetinget forsumpet fastmark Blå skravur: opphav i myr	 VM03-01 Ny torvmark på menneskebetinget forsumpet fastmark Blå skravur: opphav i myr	 VM03-01 Ny torvmark på menneskebetinget forsumpet fastmark Blå skravur: opphav i myr

VM04 Sterkt endret, ikke torvproduserende våtmark

1:50 000 · 1 enheter	1:20 000 · 1 enheter	1:5 000 · 1 enheter
 VM04-01 Sterkt endret ikke torvproduserende våtmark	 VM04-01 Sterkt endret ikke torvproduserende våtmark	 VM04-01 Sterkt endret ikke torvproduserende våtmark

VM05 Ny grunn våtmark på tidligere ferskvannsbunn

1:50 000 · 1 enheter	1:20 000 · 1 enheter	1:5 000 · 1 enheter
 VM05-01 Ny grunn våtmark på tidligere ferskvannsbunn	 VM05-01 Ny grunn våtmark på tidligere ferskvannsbunn	 VM05-01 Ny grunn våtmark på tidligere ferskvannsbunn

VM06 Ny grunn våtmark på menneskebetinget forsumpet fastmark

1:50 000 · 1 enheter	1:20 000 · 1 enheter	1:5 000 · 1 enheter
 VM06-01 Ny grunn våtmark på menneskebetinget forsumpet fastmark	 VM06-01 Ny grunn våtmark på menneskebetinget forsumpet fastmark	 VM06-01 Ny grunn våtmark på menneskebetinget forsumpet fastmark

VO01 Sterkt tråkkpreget våtmark

1:50 000 · 1 enheter



VO01-01
Sterkt tråkkpreget våtmark

1:20 000 · 1 enheter



VO01-01
Sterkt tråkkpreget våtmark

1:5 000 · 1 enheter



VO01-01
Sterkt tråkkpreget våtmark